Lagersport/Trekking

Berg



BASPO
2532 Magglingen

Schweizerische Eidgenossenschaft
Confédération suisse
Confederazione Svizzera
Confederaziun svizra

Bundesamt für Sport BASPO

Inhaltsverzeichnis

Unterwegs sein 2
Formen des Unterwegsseins 2

Vorbereitung von Wanderungen 4
Methode 3 × 3 5
SAC-Wanderwegskala 8
Routenplanung 12
Sicherheitskonzept für Unternehmungen 15

Eine Gruppe unterwegs leiten 17
Während der Aktivität 19
Faktor Mensch 22
Aktivitäten unterwegs 24
Orientierung 27
NORDA 29
Orientierungsübungen 30

Bergspezifische Gefahren 31

Ernährung 34

Ausrüstung 37

Übernachtung 43

Bergrettung 45

Glossar 51
Verwendete und weiterführende Literatur 52

Das Leiterhandbuch beinhaltet eine Reihe von Piktogrammen (Bildzeichen). Sie verweisen auf weiterführende Informationen in- und ausserhalb des Leiterhandbuchs.

Sicherheit

Kindersport

Jugendsport

Verweis auf Online-Unterlagen Lagersport/Trekking

Verweis auf weitere Unterlagen

Verweis auf Broschüren Lagersport/Trekking

Unterwegs sein

Lagersport/Trekking ermöglicht es, Wanderungen sowohl im Flachland wie auch in den Voralpen und Alpen durchzuführen. Mit dieser Broschüre wollen wir dir zeigen, wie du sie planst und durchführst. Wir wollen Gipfel erklimmen, Aussichten geniessen, Ziele erreichen, spielen, essen und übernachten. Und dies immer unter sicheren Bedingungen. Die Informationen in dieser Broschüre gelten für alle Wanderungen. Für anspruchsvolle Aktivitäten empfiehlt J+S zusätzlich das Modul Sicherheitsbereich Berg zu besuchen. Für Aktivitäten im Sicherheitsbereich ist es obligatorisch.

Merkblatt «Lagersport/Trekking – Sicherheitsanforderungen in den Bereichen Berg, Winter, Wasser»

Kinder und Jugendliche erleben nirgends so deutlich die eigenen Möglichkeiten und Grenzen wie beim gemeinsamen Unterwegssein. Sie lernen den Körper mit seinen Stärken und Schwächen kennen. Sie können ihre Fähigkeiten und Erfahrungen einsetzen und lernen, die Hilfe und Unterstützung anderer anzunehmen. Sie erhalten zudem das nötige Fachwissen, um die Herausforderungen des Unterwegsseins zu meistern. Die eigene Motivation und das Gruppenklima, die Orientierungskunst sowie etwas Mut und Überwindung helfen ebenfalls, die oft unvorhersehbaren Probleme zu lösen.

Formen des Unterwegsseins

Unterwegs zu sein, reicht als Gruppenaktivität alleine nicht aus. Es braucht ein Ziel. Dieses kann geographisch (Ortschaft, Berg usw.), dem Lagerprogramm entsprechend (Schwimmbad, Biwakplatz usw.) oder kulturell lohnend sein (Schloss, Denkmal usw.). Die Aktivität wird durch ein Thema oder eine Grundidee zum gemeinsamen Erlebnis und Ziel.

Damit eine Wanderung für Kinder attraktiv ist, ist die thematische Einkleidung ein wichtiges Element. Findet einen Grund, warum ihr unbedingt losziehen müsst. Ist euch etwas gestohlen worden, das ihr wieder finden müsst? Will euch der Zauberer hinter den Hügeln etwas zeigen, oder bekommt ihr vom Detektiv einen dringenden Auftrag? Es gibt verschiedene Möglichkeiten, unterwegs Teilaufgaben zu lösen (Spuren verfolgen/Rätsel, die gelöst werden können usw.). Wichtig ist, dass die Aufgaben für alle Kinder zugänglich sind und nicht nur für die Vordersten. Der Höhepunkt der Geschichte kann gut mit dem Höhepunkt der Wanderung kombiniert werden. Vielleicht ist der gesuchte Schatz in einem verborgenen Winkel der Ruine versteckt, die eure Wanderung krönt.

Neben der gut bekannten Wanderung gibt es auch Alternativen, die eine Wanderung interessanter machen können und so Abwechslung bieten.

Alternative Wanderformen

- **«Diretissima»:** Folgt einer Linie, der Gemeindegrenze, einer bestimmten Koordinate, einem Hügelkamm oder einer Höhenkurve möglichst ohne Abweichungen.
- **Bachtrekking:** Von der Quelle bis zum See.
  Prinzip: Bleibt immer am Fluss inkl. Schluchten usw. Achtet auf die Sicherheit. Ihr benötigt eventuell eine Anerkennung im Sicherheitsbereich Wasser.
- **Fünfliber-Lauf:** Werft bei jeder Wegkreuzung ein Geldstück auf und entscheidet, ob ihr rechts oder links gehen sollt. Nur im Mittelland oder Jura geeignet.
- **Nachtwanderung:** Ermöglicht es, die Nacht zu erleben. Achtet darauf, dass keine Angst einflössenden Elemente vorhanden sind.
- **Sternwanderung:** Von verschiedenen Ausgangspunkten aus gelangen die Gruppen zum gemeinsamen Ziel.
- **12/24-Stunden-Trekking:** Welche Gruppe kommt in 12 oder 24 Stunden am weitesten. Auch mit anderem Ziel als nur möglichst grosser Distanz möglich.
- **Wandern mit Kartenaufgaben:** nach Karte, Kroki, Beschreibungen, Spuren, Fotos, mit dem Kompass, aus dem Gedächtnis.
- **Besinnliche Wanderung:** Gebt Anstösse zum Nachdenken und Nachsinnen. Pilgern ist eine der ältesten Formen des Wanderns.
- **Einkleidung:** Wandern nach einer Fortsetzungsgeschichte oder mit einer Schatzkarte.

Vorbereitung von Wanderungen

Bevor du mit der Tourenplanung startest, musst du wissen, welche Art Tour du mit deinen Teilnehmenden durchführen willst. Denn je nach Ziel planst du anders: Eine einfache Wanderung im Mittelland stellt andere Anforderungen als die Besteigung eines Gipfels in den Alpen und ein Bachtrekking ist etwas anderes als eine Bergwanderung.

Folgende Fragen helfen dir, eine geeignete Wanderung auszuwählen:

- Was möchte ich mit dieser Wanderung erreichen? Was sind meine Ziele?
- Welche Art von Tour entspricht den Bedürfnissen der Teilnehmenden? Was ist altersgerecht? Wie viel Erfahrung haben die Teilnehmenden?
- Bei welchen Unternehmungen kann ich die Verantwortung für die Gruppe übernehmen und die Risiken für mich und die Teilnehmenden richtig einschätzen?
- Über welches Wissen verfüge ich und welche Erfahrung habe ich? Welche zusätzlichen Leitenden können mitkommen?
- Wie sind die Verhältnisse? Wie fit ist die Gruppe? Was ist unter diesen Bedingungen machbar?
- Welche Alternativen gibt es zur geplanten Tour? Vom gleichen Ausgangspunkt? Wohin kann ich ausweichen?

Beim Wandern mit Kindern soll nicht die Leistung im Vordergrund stehen. Die Kinder sollen durch Erlebnisse in der Natur, Abenteuer und Bewegung die Freude am Wandern entdecken. Die effektive Wanderzeit sollte deshalb nicht länger als 2 bis 3 Stunden sein.

Methode 3 × 3

Bei der Planung musst du deine Kenntnisse über die Verhältnisse, das Gelände und die Gruppe sowie deren Zusammenspiel mit deinem eigenen Wissen und Können abstimmen. Du musst dir zutrauen, die Tour unter den gegebenen Umständen zu leiten.

Broschüre «Grundlagen», Kapitel «3 × 3»

Eine gute Planung verschafft dir einen Sicherheitsvorsprung. Die Methode 3 × 3 hilft dir bei der Vorbereitung und sicheren Durchführung der Aktivität. Sie verbindet die Vorbereitung zu Hause mit der rollenden Planung unterwegs und hilft, Entscheidungen zu treffen, die alle relevanten Faktoren berücksichtigen.

Das für alle Aktivitäten gültige Raster der Methode 3 × 3 wird in der Broschüre «Lagersport/Trekking – Grundlagen» vorgestellt. In dieser Broschüre wird das Raster für die verschiedenen Zeitpunkte durch bergspezifische Punkte ergänzt.

Merkblatt «Lagersport/Trekking – 3 × 3 – unterwegs sein», Planung

Verhältnisse

Im Frühling und im Frühsommer musst du in höheren Lagen (über ca. 2000 m) noch mit Altschnee rechnen. Deshalb eignen sich für diese Jahreszeit vor allem Wanderungen an Fluss- und Seeufern im Mittelland oder im hügeligen Gelände des Juras und der Voralpen.

Im Sommer musst du – insbesondere in tieferen Lagen – die Hitze beachten. Meide weite Ebenen und Aufstiege an südexponierten Hängen. In den Alpen ist der Sommer die ideale Zeit für Touren. Viele Touren können auch nur in dieser Jahreszeit rekognosziert werden. In den Bergen treten im Sommer am Nachmittag oft Gewitter auf. Plane die rechtzeitige Rückkehr.

Im Herbst hat man an schönen Tagen oft eine herrliche Fernsicht. Ab Oktober kann aber bei schlechtem Wetter in höheren Lagen schon Schnee liegen. Ebenso wird es bereits wieder früher dunkel.

Für Wanderungen im Winter gelten die Bestimmungen des Sicherheitsbereichs Winter. Genaueres dazu findest du in den Broschüren «Lagersport/Trekking – Winter», auf dem Merkblatt «Berg, Winter, Wasser: Abgrenzung Normal-/Sicherheitsbereich» sowie im Leitfaden.

Merkblatt «Lagersport/Trekking – Sicherheitsanforderungen in den Bereichen Berg, Winter, Wasser»

Gelände

Die Route muss in der Vorbereitung anhand der Karte möglichst genau geplant werden. Beachte beim Einzeichnen des Weges auf der Karte, dass du keine relevanten Informationen überdeckst. Kennzeichne markante Punkte und die Stellen, an denen der Weg von Aufstieg zu Abstieg oder umgekehrt wechselt. Diese Informationen dienen dir als Grundlage zur Marschzeitberechnung. Mach dir bereits vor dem Rekognoszieren ein Bild der Route und versuche die Schlüsselstellen und Umkehr- bzw. Entscheidungspunkte der Tour zu definieren. Beim Rekognoszieren kannst du deine Vorstellung überprüfen und die Planung allenfalls anpassen.

Schlüsselstellen sind die schwierigsten Teile einer Unternehmung, die besondere Vorsichtsmassnahmen erfordern. Beispiele von Schlüsselstellen sind exponierte Passagen mit Absturzgefahr, die Überquerung einer stark befahrenen Strasse mit Kindern oder der Abstieg über ein steiles Schneefeld.

Umkehr- und Entscheidungspunkte sind diejenigen Stellen einer Unternehmung, an denen du entscheiden musst, ob die geplante Route unter den gegebenen Umständen durchgeführt werden kann. Falls nicht, musst du eine Alternative wählen oder umkehren. Diese Punkte sind oft an Abzweigungen zwischen zwei Varianten. Sie können aber auch zeitlich definiert sein, wenn sonst nicht mehr genügend Zeit für die gesamte Unternehmung bleibt (z. B. spätestens um 15 Uhr umkehren, egal ob der Gipfel erreicht ist).

Faktor Mensch/Material

Überlege dir, wer alles auf die Tour mitkommen wird und welche Erfahrung diese Personen mitbringen. Im Normalfall passt du besser die Tour der Gruppe an als umgekehrt. Falls nicht alle mitkommen können, musst du dir für die Zurückbleibenden ein Alternativprogramm überlegen. Aus den Überlegungen zur Gruppe ergibt sich auch der Geschwindigkeitsfaktor, der zur Zeitberechnung verwendet wird.

Eine Gruppe unterwegs zu leiten, verlangt von dir als Leiterperson nicht nur sportarttechnisches Können und Wissen, sondern auch Führungskompetenzen. Jede Leiterin und jeder Leiter muss sein eigenes Können und auch das Verhalten der einzelnen Gruppenmitglieder richtig einschätzen können. Ein geübtes Auge für gruppendynamische Prozesse hilft, allfällige Konflikte zu erkennen und notfalls zu intervenieren. Ein der Situation angepasster Umgang mit gruppendynamischen Prozessen ist auf einer Wanderung sicherheitsrelevant.

Nur durch viel praktische Erfahrung und verinnerlichtes Wissen kannst du dir alle Fähigkeiten aneignen, die zur Leitung einer **anspruchsvollen** Wanderung notwendig sind:

- Persönliche Belastbarkeit und ein ausgeprägtes Mass an Flexibilität, um auch ungewohnte Situationen zu meistern.
- Rasch Entscheidungen treffen und durchsetzen können.
- Bergerfahrung: Die verantwortliche Leiterperson muss im Gebirge mehrere anspruchsvollere Touren unternommen haben.
- Ausgeprägtes Verantwortungsbewusstsein.
- Sozialkompetenz: Zwischenmenschliche Spannungen wahrnehmen, auf andere eingehen und mit anderen angemessen umgehen können.
- Sehr gute körperliche Verfassung und Ausdauer.
- Gute sportarttechnische Fähigkeiten (Orientierung im Gelände, Umgang mit Karte und Kompass, Abkochen und Übernachten im Freien).

Eine anspruchsvolle Wanderung sollte mindestens von einem Zweierteam geleitet werden. Dadurch könnt ihr Verantwortlichkeiten aufteilen und im Falle einer Erkrankung oder eines Unfalls ist eine zweite Leiterperson vorhanden, welche die Risiken einschätzen und die Fortsetzung der Wanderung gewährleisten kann.

Die Geschlechter, die in der Gruppe vertreten sind, sollten sich im Leitungsteam widerspiegeln. Auf diese Weise können sich die Teilnehmenden mit geschlechterspezifischen Fragen oder Problemen an eine Person des eigenen Geschlechts wenden.

SAC-Wanderwegskala

Bei der Planung einer Wanderung zu Hause stellt sich immer die Frage, wie schwierig sie ist und ob man den Anforderungen gewachsen ist. Die SAC-Wanderwegskala hilft bei der Beurteilung der zu erwartenden Schwierigkeiten. Sie beschreibt die Merkmale der verschiedenen Wege. Für die Schwierigkeitsangabe wird jeweils die anspruchsvollste Stelle einer Wanderung oder Etappe bewertet.

Die Touren im Bereich des Berg- und Alpinwanderns werden jeweils unter der Annahme günstiger Verhältnisse bewertet, also bei guter Witterung und Sicht und trockenem Gelände. Bei schlechten Bedingungen kann eine leichte T2-Tour rasch schwieriger werden.

Wegmarkierungen im Gelände

Die Schweizer Wanderwege verwenden zur Markierung der Routen drei Farbkombinationen. Der Schwierigkeitsgrad lässt sich nicht direkt ablesen, aber als grobe Faustregel gelten die Angaben in der folgenden Tabelle.

Wegweiser/Farbmarkierung	Wegbezeichnung	Schwierigkeit
gelb	Wanderweg	T1
weiss-rot-weiss	Bergwanderweg	T2 bis T3
weiss-blau-weiss	Alpinwanderweg	T4 bis T5

T1 – Wandern

Weg-/Geländemerkmale Weg gut gebahnt. Falls vorhanden, sind exponierte Stellen sehr gut gesichert. Absturzgefahr kann bei normalem Verhalten weitgehend ausgeschlossen werden.

Anforderungen Gering, auch mit Turnschuhen geeignet. In der Regel einfache Orientierung.

Geeignet für Kinder und Jugendliche.

T2 – Bergwandern

Weg-/Geländemerkmale Weg mit durchgehendem Trassee. Gelände teilweise steil, Absturzgefahr nicht ausgeschlossen.

Anforderungen Etwas Trittsicherheit. Trekkingschuhe. Durchschnittliches Orientierungsvermögen.

Geeignet für Kinder und Jugendliche.

T3 – anspruchsvolles Bergwandern

Weg-/Geländemerkmale Weg am Boden nicht unbedingt durchgehend sichtbar. Ausgesetzte Stellen können mit Seilen oder Ketten gesichert sein. Eventuell braucht man die Hände fürs Gleichgewicht. Zum Teil exponierte Stellen mit Absturzgefahr, Geröllflächen, weglose Schrofen.

Anforderungen Gute Trittsicherheit. Gute Wanderschuhe. Gutes Orientierungsvermögen. Elementare alpine Erfahrung.

Geeignet für Jugendliche.

T4 – Alpinwandern

Weg-/Geländemerkmale Wegspur nicht zwingend vorhanden. An gewissen Stellen braucht es die Hände zum Vorwärtskommen. Gelände bereits recht exponiert, heikle Grashalden, Schrofen, einfache Firnfelder und apere Gletscherpassagen.

Anforderungen Vertrautheit mit exponiertem Gelände. Gute Wanderschuhe oder Bergschuhe. Gewisse Kenntnisse für Geländebeurteilung und gutes Orientierungsvermögen. Alpine Erfahrung. Bei Wetterumsturz kann ein Rückzug schwierig werden.

Geeignet für Ausserhalb von Lagersport/Trekking.

T5 – anspruchsvolles Alpinwandern

Weg-/Geländemerkmale Oft weglos. Einzelne einfache Kletterstellen. Exponiert, anspruchsvolles Gelände, steile Schrofen. Apere Gletscher und Firnfelder mit Ausrutschgefahr.

Anforderungen Bergschuhe. Sichere Geländebeurteilung und sehr gutes Orientierungsvermögen. Gute Alpinerfahrung auch im hochalpinen Gelände. Elementare Kenntnisse im Umgang mit Pickel und Seil.

Geeignet für Ausserhalb von Lagersport/Trekking.

T6 – schwieriges Alpinwandern

Weg-/Geländemerkmale Meist weglos. Kletterstellen bis II. Häufig sehr exponiert. Heikles Schrofengelände. Apere Gletscher mit erhöhter Ausrutschgefahr.

Anforderungen Ausgezeichnetes Orientierungsvermögen. Ausgereifte Alpinerfahrung und Vertrautheit im Umgang mit alpintechnischen Hilfsmitteln.

Geeignet für Ausserhalb von Lagersport/Trekking.

Routenplanung

Planungsunterlagen für Wanderungen
Folgende Unterlagen musst du deinem Coach für jede Wanderung zur Verfügung stellen:
- Kartenkopie mit geplanter Route.
- Marschzeitberechnung (Vorlage auf J+S-Webseite).
- Sicherheitskonzept.
- Evtl. Fotos vom Rekognoszieren

map.geo.admin.ch
wanderland.ch
hikr.org
Websites von SAC-Hütten

Die Planung beginnt mit der Wahl einer geeigneten Tour. Dafür stehen dir verschiedene Informationsquellen zur Verfügung:
- Wanderführer (z. B. SAC-Reihe Alpinwandern).
- Landeskarte/Wanderkarte/map.geo.admin.ch
- Internet-Recherchen (wanderland.ch, hikr.org, Websites von SAC-Hütten).
- Luftbilder.
- Lokale Auskunftspersonen (Vermieter, Hüttenwarte, Tourist-Info).
- Eigene Gebietskenntnisse.

Hast du eine interessante Tour gefunden, kannst du mit folgenden Fragen bestimmen, ob sie für deine Gruppe in Frage kommt:
- Stellt die Tour ein Ziel dar, für das sich die Teilnehmenden motivieren lassen? Lässt sich die Tour mit einer anderen Aktivität verbinden (Schwimmbadbesuch, Sehenswürdigkeit, Aussichtspunkt, Biwak, andere LS/T-Aktivität)? Bietet die Wanderung genügend Abwechslung (keine monotonen Wege, unterschiedliches Gelände, auf und ab)?
- Entspricht der Schwierigkeitsgrad deinem Können und dem der Gruppe?
- Gibt es geeignete Alternativen, falls die Tour aufgrund der Umstände nicht durchgeführt werden kann (Wetter, Tagesverhältnisse)? Kannst du die Tour innerhalb des Lagers falls nötig verschieben?
- Ist die Tour mit vertretbarem logistischem Aufwand machbar (möglichst kurze Anreise und Rückreise, keine übermässig teuren Transportmittel notwendig, mit öffentlichem Verkehr erreichbar)?

Rekognoszieren

Das Rekognoszieren hilft dir, das Gelände und mögliche Gefahrenstellen schon vor der Wanderung zu kennen. Ein Bach oder ein steiler Abhang, der mit wandererfahrenen Jugendlichen kein Problem ist, könnte mit Kindern gefährlich werden, weil diese die Situation weniger gut einschätzen können. Dank des Rekognoszierens kannst du entscheiden, ob eine Wanderung allenfalls schon zu schwierig ist oder ob du dir die Durchführung mit deiner Gruppe zutraust. Du erhältst auch die Sicherheit, in heiklen Momenten oder bei einem Wetterumschwung bessere Entscheidungen zu treffen. Du weisst, wo die Schlüsselstellen sind und wo du besser umkehren oder allenfalls weitergehen kannst. Rekognosziere wenn ungefähr die gleichen Bedingungen herrschen, die du im Lager vorfindest. Allerdings ist es nicht empfehlenswert, eine Wanderung erst kurz vor der Durchführung zu erkunden, da dann oft keine Möglichkeit mehr besteht, Alternativen zu testen. Für anspruchsvolle Wanderungen und falls die Bedingungen wesentlich anders sind als zum Zeitpunkt des Rekognoszierens, lohnt es sich, die Schlüsselstellen der Wanderung kurz vor oder während des Lagers nochmals genauer anzuschauen.

- Wanderungen in den alpinen und voralpinen Gebieten, im Jura sowie im Ausland müssen rekognosziert werden.
- Bei ähnlichen Bedingungen (Jahreszeit, Tageszeit) rekognoszieren.
- Gründliches Rekognoszieren gibt dir einen Sicherheitsvorsprung.
- Bei Unklarheiten über die aktuellen Bedingungen (Schnee, Zustand des Weges) kurz vor oder im Lager nochmals die Schlüsselstellen begutachten.
- Auf folgende Dinge besonders achten:
  - Schlüsselstellen.
  - Mobilfunkempfang.
  - Trinkwasser.
  - Geeignete Pausenplätze.
  - Passagen mit anspruchsvoller Orientierung.
  - Mögliche Abkürzungen.
  - Effektive Marschzeit.

Zeitberechnung

Die Grundlage für die Berechnung der Marschzeit einer Wanderung bildet immer die Länge der Wanderung in Leistungskilometern (Lkm) und die voraussichtliche Marschgeschwindigkeit.
1 Leistungskilometer entspricht:
- 1 Kilometer Horizontaldistanz.
- 100 Höhenmeter Steigung.
- 150 Höhenmeter starkes Gefälle.

Folgende Richtgrössen für den Zeitfaktor (Lkm pro Stunde ohne eingeplante Pausen) haben sich in der Praxis bewährt:

Gruppe	Mit Gepäck	Ohne Gepäck
Untrainierte Gruppe, Kinder, grosse Gruppe	2–4 Lkm/h	3–5 Lkm/h
Trainierte Gruppe, Jugendliche, kleine Gruppe	3–5 Lkm/h	4–6 Lkm/h

Die Marschgeschwindigkeit hängt jedoch von vielen Faktoren ab:

Faktor	Schneller	Langsamer
Gruppengrösse	Klein	Gross
Tageszeit	Morgen	Nachmittag, Abend
Wetter	Kühl	Heiss
Gepäck	Wenig	Viel
Wege	Gute Wege	Geröllfelder, querfeldein, schmale oder steile Wege
Fitness	Ausgeschlafen, satt, alle gleich trainiert und motiviert	Müde, hungrig, ungleich trainiert oder unmotiviert
Orientierung	Gute Kartenkenntnisse, einfache Orientierung	Häufige Kartenkontrollen, schwierige Orientierung (z. B. Nebel)

Vorlage «Zeitberechnung/Höhenprofil»

Fülle zur Berechnung der Marschzeit am besten eine Marschtabelle aus. Du kannst eine elektronische Vorlage mit eingebauten Berechnungsformeln von der J+S-Webseite herunterladen.

Neben der reinen Marschzeitberechnung musst du dir auch einen Zeitplan für den gesamten Tag erstellen. Plane dabei Reservezeiten und Pausen ein. Zur sinnvollen Pausenplanung findest du Hinweise im Kapitel «Eine Gruppe unterwegs leiten» (S. 17). Je anspruchsvoller eine Tour ist, desto mehr Reserve musst du einplanen. Definiere bei einer Gipfelbesteigung auch, zum welchem Zeitpunkt ihr spätestens umkehrt, egal ob das Ziel erreicht ist oder nicht. Plane zudem bei Wanderungen mit Kindern lieber zu viel Zeit ein und fülle die Zeit dann allenfalls mit Kurzspielen aus.

Zeitfresser
- Anspruchsvolle Stellen, sobald es die Hände braucht.
- Unübersichtliche Orientierung, Verlaufen, weglose Abschnitte, schlechte Sicht.
- Schneefelder.
- Geröllfelder, Karstfelder.
- Teilnehmende mit Leistungsproblemen (Blasen, Müdigkeit).
- Schlechte oder defekte Ausrüstung (Schuhe).
- Unorganisierte Gruppe (grosse Abstände, unklare Führung, ständiges Anhalten, «Handorgel-Effekt»).

Sicherheitskonzept für Unternehmungen

Die zentralen Fragen, die du dir für dein Sicherheitskonzept stellen musst, werden in der Broschüre «Lagersport/Trekking – Grundlagen» erläutert. In diesem Kapitel geht es deshalb noch darum, die Fragen für Wanderungen zu konkretisieren.

Basierend auf der Gefahrenanalyse und den Schlüsselstellen muss das Sicherheitskonzept folgende Fragen beantworten:

Frage 1

Welche Massnahmen kann ich ergreifen, um den erkannten Gefahren entgegenzuwirken?

- Verantwortung innerhalb des Leitungsteams klären (Zuständigkeiten, Rollen).
  - System Pilot/Kopilot (S.18 – Leiterpersonen).
  - Schlusslicht.
- Alternative Varianten und Abbruchkriterien definieren.
  - Entscheidungskriterien zur Durchführung der Tour und zur Begehung der einzelnen Schlüsselstellen.
  - Zeitpunkt, bei dem spätestens umgekehrt werden muss (ohne das Ziel erreicht zu haben).
  - Kriterien für alle drei Faktoren des 3 × 3 definieren.
  - Wo sind mögliche Umkehr- und Ausstiegspunkte? «Point of no return»?
  - Gibt es unterwegs Unterstände oder Übernachtungsmöglichkeiten?
  - Welche Abkürzungen oder alternativen Routen sind möglich?
  - Alternativprogramm bei Schlechtwetter.
- Sicherheitsrelevante Verhaltensregeln und klare Grenzen definieren.
  - Welche Regeln gelten für das Verhalten der Teilnehmenden und Leiter (Zusammenbleiben, Leiter an der Spitze, Konzentration auf Weg)? Was geschieht, wenn sich jemand nicht daran hält?
  - Mit welchen zusätzlichen Massnahmen kann eine Schlüsselstelle entschärft werden (geeignete Routenwahl, Hilfestellung durch Leitende, Reduktion oder Abnehmen des Gepäcks, Pause vor der Schlüsselstelle)?
- Angemessene Ausrüstung für Teilnehmende und Leitung sicherstellen und nur funktionstüchtiges und sicheres Material verwenden.
  - Über welche Ausrüstung müssen Leitende und Teilnehmende verfügen (Schuhe, Kleidung, Rucksack, Proviant, Erstehilfeausrüstung, Mobiltelefon)?
  - Welche Hilfsmittel können eingesetzt werden (Kompass/GPS für Orientierung)?
- Weitere aktivitäten-spezifische Massnahmen wie das Einhalten gewisser Sicherheitsstandards (SLRG-Baderegeln, fünf Grundregeln Winter).

Frage 2

Wie kann ich mich auf allfällige Notfallsituationen vorbereiten?

- Alarmierungsmöglichkeiten bei der Rekognoszierung abklären.
  - Besteht Mobilfunkempfang? Wo sind «Funklöcher»?
  - Ist ein Notfunkgerät notwendig? «Walkie-Talkies» zur Kommunikation unter den Wandergruppen?
  - Wo gibt es ein Festnetztelefon (SAC Hütte, evtl. Alphütte)?
- Ablauf im Notfall klären (Vorgehen und Rollenverteilung).
  - Wer alarmiert?
  - Wer betreut Verletzte?
  - Wer betreut die anderen Teilnehmenden?
- Notfallmaterial bereithalten.
  - Notfallapotheke für jede Wandergruppe.
  - Geladenes Mobiltelefon oder Notfunkgerät zur Alarmierung, Liste der Notrufnummern und Telefonnummern der Leiter.
  - Wer hat zusätzliches Notfallmaterial für die gesamte Gruppe dabei? Wer hat das Notfunkgerät?
- Eine Person (J+S-Coach), die nicht an der Wanderung teilnimmt, über das Vorhaben informieren (schriftliche Routenplanung, TN-Liste).

Um eine sichere Aktivität durchzuführen, muss allen Leitern das Sicherheitskonzept auch während der Durchführung präsent sein und sie müssen sich daran orientieren. Besprecht das Konzept kurz vor der Durchführung nochmals im Team. Gib es allen Leitern in schriftlicher Form ab.

Wann ist ein Sicherheitskonzept notwendig?

- Für alle Aktivitäten in einem Sicherheitsbereich.
- Für anspruchsvolle Bergwanderungen.

Für alle anderen Wanderungen wird ein (kurzes) Sicherheitskonzept empfohlen.

Ein Sicherheitskonzept basiert auf der Einschätzung der Gefahren. Die Methode 3 × 3 hilft dir, alle relevanten Gefahren zu erkennen. Im Sicherheitskonzept beschreibst du die Schlüsselstellen einer Unternehmung und die Taktik, wie du sie bewältigen willst.

Eine Gruppe unterwegs leiten

Bist du am Startpunkt der Wanderung angelangt, gilt es mit Hilfe des 3 × 3 die aktuelle Situation zu beurteilen.

Merkblatt «Lagersport/Trekking: 3 × 3 – unterwegs sein», Vor Ort

Siehst du nach deiner Situationsanalyse neue Gefahren, musst du deine Massnahmen anpassen. Denn ab jetzt bist du mit der Gruppe unterwegs und für ihre Sicherheit und das Gruppenerlebnis verantwortlich.

Leitungsstile

Leitungsstile beschreiben dein Verhalten als Leiter. Du beeinflusst damit den Erfolg der ganzen Aktivität. Ein situationsangepasster Leitungsstil ist Voraussetzung.

Klarer Leitungsstil

Ein klarer Leitungsstil ist immer dann angebracht, wenn sich aus Sicherheitsgründen alle an bestimmte Regeln und Verhaltensweisen halten müssen. Dann gibst du als Leiter die Regeln vor und kontrollierst deren Einhaltung. Es hilft, wenn du die Regeln im Voraus klar besprichst, und die Teilnehmenden verstehen, warum sie eingehalten werden müssen. Zum Beispiel wird im Absturzgelände hintereinander und nicht nebeneinander gewandert. Wenn es das Gelände und die Sicherheit erlauben, kannst du einen Leitungsstil wählen, der die Teilnehmenden in Entscheidungen mit einbezieht. Dies fördert selbständiges und verantwortungsbewusstes Handeln. Ihr könnt beispielsweise gemeinsam bestimmen, ob ein Abstecher auf einen Gipfel gemacht oder direkt weitergewandert wird.

Offener Leitungsstil

Ein offener Leitungsstil lässt den Teilnehmenden viel Freiraum für individuelle Interessen und Tätigkeiten. Dies eignet sich beispielsweise nach der Ankunft auf einem Biwakplatz. Auf anspruchsvollen Bergwanderungen hat dieser Leitungsstil jedoch nichts verloren.

Überlege dir vor einer Wanderung jeweils, wann du welchen Leitungsstil wählen kannst.

PraxisTIPPS

- Leichte, übersichtliche Wege mit eindeutiger Wegführung erlauben eine lose Gruppenordnung mit grösseren Abständen zwischen den Teilnehmenden.
- Unübersichtliches Gelände oder eine schlechte Wegmarkierung erfordern Sichtverbindung zwischen allen Teilnehmenden.
- Schlechte Sicht (Nebel, Schneefall, Neuschnee auf Markierungen) verlangt ein aufgeschlossenes Gehen mit Übersicht über die ganze Gruppe.
- Für den Fall, dass sich die Gruppe auseinander zieht, müssen sinnvolle Treffpunkte und Zeiten abgemacht und kommuniziert werden.
- Informiere deine Gruppe regelmässig: Wann gibt es die nächste Pause, wo sind wir jetzt usw.

Die Leitenden

Innerhalb des Leitungsteams – bei Wanderungen sollte es mindestens ein Zweierteam sein – ist es sinnvoll, dass man sich aufteilt: Jemand übernimmt die Rolle des «Piloten», die andere Person diejenige des «Kopiloten». Der «Pilot» übernimmt die Führungs- und Orientierungsarbeit, der «Kopilot» kontrolliert mit seiner Karte, denkt laut mit, berät sich allenfalls mit dem «Piloten». Schon während der Vorbereitungsphase können solche Zweierteams Marschtabelle und Streckenprofil für «ihre» Tagesetappe erstellen.

Sind mehr als zwei Leitende auf der Wanderung dabei, können diese als «Flight Attendants» eingesetzt werden: Sie kümmern sich um kleinere Probleme der Teilnehmenden selbständig und melden grössere Dinge dem «Piloten», der den Überblick über die Wanderung und Gruppe hat.

Jemand des Leitungsteams muss auf jeden Fall die Rolle des Schlusslichts übernehmen. Diese Person kennt idealerweise den Weg bereits und ist in der Lage, diesen auch selbst zu finden.

Die Gruppe

Mach dir vor einer Wanderung mit deinem Leitungsteam Gedanken, wie ihr die Gruppe organisieren wollt, damit ihr jedem einzelnen Kind und Jugendlichen ein gutes Wandererlebnis bieten könnt. Manchmal ist es sinnvoll, kleine Gruppen zu bilden, die aus etwa gleich leistungsfähigen Teilnehmenden bestehen. Jede Gruppe kann dann in ihrem eigenen Marschtempo unterwegs sein. Sie werden jeweils von einer Leitersperson geführt, die über die nötige fachtechnische Kompetenz verfügt und mit dem nötigen Karten- und Erste-Hilfe-Material ausgerüstet ist.

Check vor dem Loslaufen

Bevor ihr loswandert, solltest du verschiedene Dinge überprüfen: Kontrolliert, ob ihr alles mit dabei habt (siehe Merkblatt «3 × 3 – Unterwegs sein»). Insbesondere bei Kindern, aber auch bei Jugendlichen, ist Folgendes zu beachten:

- WC besucht falls nötig?
- Schuhe gut geschnürt?
- Angemessene Kleidung?
- Alle mit Sonnenschutz (Sonnencrème, Sonnenhut) ausgerüstet?
- Nicht zu grosser, gut eingestellter Rucksack?
- Alles eingepackt (siehe «Ausrüstungsliste auf dem Merkblatt 3 × 3 unterwegs sein»)?
- Gesundheitlicher Zustand der Teilnehmenden und Leitenden?
- Kinder zählen

Dieser Check hilft dir den Überblick zu gewinnen. Hat es Teilnehmende dabei, die ungenügend ausgerüstet sind, kannst du nachhelfen, bevor ihr unterwegs seid.

Während der Aktivität

Unterwegs liegt es an dir als Leiterperson, in regelmässigen Abständen die Situation neu zu beurteilen. Dabei helfen dir die folgenden Fragen.

Merkblatt «Lagersport/Trekking: 3 × 3 – unterwegs sein», während der Aktivität

Aufgrund deiner Beurteilung bist du möglicherweise gezwungen, Änderungen in der Gruppenleitung vorzunehmen. Deine Entscheidungen werden von psychologischen Faktoren beeinflusst, welche die Wahrnehmung beeinflussen können. Der Mensch neigt dazu, das wahrzunehmen, was er erwartet und was er will. Häufig tendiert er dazu, nur die Informationen zu verwenden, die seine vorgefasste Meinung bestärken.

Weitere hilfreiche Tipps zum Treffen von guten Entscheiden – auch unpopulären – findest du in der Broschüre Winter.

Broschüre «Winter», Kapitel «Entscheidungen fällen, Faktor Mensch, Beeinflussung der Wahrnehmung»

Marschtempo

Das Marschtempo ist oft ein entscheidender Faktor für den Erfolg einer Wanderung. Merke dir deshalb folgende Punkte:

1. Das Tempo richtet sich grundsätzlich nach dem Schwächsten. Es erlaubt der Gruppe, das bewusste Gehen im Gebirge richtig anzuwenden und die Umwelt wahrzunehmen.
2. Solange die Teilnehmenden noch miteinander sprechen können, stimmt das Marschtempo. Achte auf Teilnehmende, die das nicht mehr können.
3. Gliedere die Etappe in Phasen.
   - Phase 1: Gemächlich einlaufen (ca. 15 Minuten). Der Körper muss sich zuerst an eine Leistung gewöhnen. Ein kurzer Halt gibt allen die Möglichkeit, um Rucksäcke nachzustellen und Schuhe besser zu schnüren oder warme Kleider auszuziehen.
   - Phase 2: Tempo etwas steigern, auf gute und regelmässige Atmung achten (durch die Nase).
   - Phase 3: Auslaufen mindestens fünf Minuten vor dem Halt. Dieser wird somit in entspanntem Zustand erreicht (kein Schweissausbruch).
   - Phase 4: Der Halt – nun kann sich der Körper wirklich erholen.

Die meisten Anfänger laufen zu schnell los.

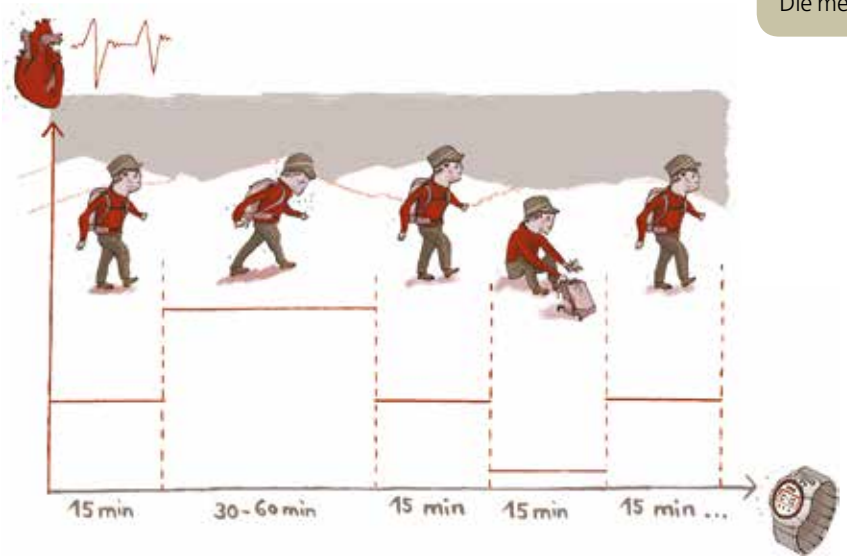

Der erfahrene Wanderer startet leicht fröstelnd.

Mit einem geeigneten Marschtempo trägst du auch wesentlich zur Temperaturregulierung des Körpers bei. Ziehe Kleider nicht erst aus, wenn du schwitzt, sondern schon vorher. Wird es kälter oder legst du eine Pause ein, ziehe dich sofort wieder an.

Pausen

Unregelmässige Unterbrechungen der Belastung wirken sich negativ auf die Leistungsfähigkeit im Ausdauerbereich aus. Andererseits sind jedoch ausreichende Pausen zur Erholung, zum Essen und zum Trinken erforderlich. Nicht zuletzt sollten beim Bergwandern auch längere Pausen eingeplant werden, um die Natur zu geniessen.

PraxisTIPPS

- Wähle den Ort der Pause so, dass du den weiteren Verlauf der Route überblicken kannst. Empfehlenswert ist ein eher ebenes Gelände (schöne Aussicht, genügend Platz, langsamer Beginn für das Weiterwandern). Dies kannst du sehr gut aus dem Höhenprofil lesen.
- Die Pausenzeit beginnt, wenn alle Gruppenmitglieder eingetroffen sind. So haben auch die Langsamsten genügend Pause.
- Kürzere Pausen als eine Viertelstunde sind nicht sinnvoll. Der Körper braucht genügend Zeit, um sich zu erholen und die Energiereserven wieder aufzufüllen. Plane lieber weniger Pausen, dafür genügend lange.
- Halte unvermeidbare Unterbrechungen während einer Belastungsphase möglichst kurz (unter zwei Minuten).
- Fasse jeweils mehrere notwendige Tätigkeiten zusammen, um die Anzahl der Unterbrechungen zu verringern (z. B. eincremen, fotografieren und trinken).
- Nutze die Pause für Erkundungen des weiteren Weges, falls du plötzlich unsicher bist.
- Die Pause bietet gute Gelegenheit zur Informationsbeschaffung: Frage bei den Teilnehmenden nach, ob mit den Schuhen (Blasen, Gelenke) oder dem Rucksack (etwas drückt in den Rücken) alles in Ordnung ist und versuche einzuschätzen, in welcher Verfassung die Gruppe und die einzelnen Personen sind.

Plane mit Jugendlichen die erste grössere Rast etwa zwei Stunden nach der Einlaufphase ein. Dafür sind mindestens 20–30 Minuten für die körperliche Erholung, das Essen und Trinken einzurechnen. Weitere Pausen folgen etwa im Stundenrhythmus. Bei hoher Belastungsintensität ist die Zufuhr von Flüssigkeit und Nahrung in kürzeren Abständen sinnvoll. Kinder brauchen mehr, dafür kürzere Pausen. Sie sind schneller müde, dafür erholen sie sich auch schneller als Jugendliche und Erwachsene. Plane darum jede Stunde eine Pause ein. Während dieser sollen sich die Kinder beim freien Spiel erholen oder die Natur beobachten können. Achte in den Pausen auch darauf, dass die Kinder genug trinken und essen. Sie können weniger Flüssigkeit und Energie speichern als Jugendliche und Erwachsene. Es ist deshalb gut, wenn du als Leiterperson mit den Kindern isst und trinkst.

Broschüre «Spiel und Sport»,
Kapitel «Spiel und Sport im Programm»

Abstieg

Die Leiterpersonen müssen bei Abstiegen besonders aufmerksam sein. Denn die meisten Bergunfälle ereignen sich während des Abstiegs. Dies geschieht aus folgenden Gründen:

- Der Höhepunkt der Tour ist vorbei, die Gruppe ist euphorisch, das Ziel erreicht zu haben. Der Abstieg wird deshalb oft unterschätzt. Auch bei der Tourenplanung geht dieser Teil häufig vergessen.
- Der Abstieg führt oft durch scheinbar «leichtes Gelände». Es kann unterschätzt werden, was für die Leiterpersonen eine zusätzliche Herausforderung darstellt.
- Die Konzentration lässt wegen der Ermüdung nach.
- Viele Stellen sind im Abstieg schwieriger als im Aufstieg.
- Das Ausrutschen hat häufig grössere Konsequenzen (längerer Bremsweg).

PraxisTIPPS

- Plane reichlich Zeit für den Abstieg ein.
- Betreue und sensibilisiere die Gruppe auf dem Gipfel: «Für den Abstieg müssen wir uns alle nochmals voll konzentrieren».
- Organisiere vorausblickend: Leistungsgruppen, Gruppengrösse, Abstände usw.
- Achte darauf, dass beim Abwärtsgehen niemand den Oberkörper nach hinten lehnt (Rutschgefahr).
- Zur Kraftersparnis und zur Schonung der Gelenke sollten gerade bei steilen Abstiegen die Schritte klein gehalten werden.

Faktor Mensch

Unter dem «Faktor Mensch» werden alle Merkmale der Teilnehmenden und Leitenden zusammengefasst. Als J+S-Leiterperson bist du mit Kindern und Jugendlichen unterwegs:
- Sie sind spontan, auch einmal überschäumend, noch nicht abgeklärt.
- Du bist für die dir anvertrauten Teilnehmenden verantwortlich.
- Du bist für die Gruppe ein Vorbild, das gerne kopiert wird.

Schaffe dir deshalb eine Sicherheitsreserve. Achte bewusst mehr als üblich auf die Sicherheit. Setze Anordnungen durch, die du als richtig erachtest, unabhängig davon, wie sich andere Gruppen und Touristen verhalten. Als Leiterperson musst du dich immer im Komfortbereich bewegen: Du darfst nie überfordert sein.

Gruppenklima und Emotionen

Der Erfolg deiner Wanderung oder deines Bergtrekkings hängt neben den bisher erwähnten Faktoren auch vom Gruppenklima ab. Ein gutes Gruppenklima ist geprägt von gegenseitiger Wertschätzung und Anerkennung. Dies bedeutet:
- Teilnehmende und Leitende unterstützen sich gegenseitig.
- Kritikfähigkeit: Fehler und Schwächen können eingestanden werden.
- Die schwächste Person wird «mitgetragen».
- Die Mitglieder wachsen über sich selbst hinaus, erstaunliche Leistungen werden möglich.
- Erleben einer Gemeinschaft.

Lasse den Kindern und Jugendlichen unterwegs Freiräume, die sie selbst gestalten können – zum Beispiel in Pausen oder am Abend. Dies hilft bei ihrer Entwicklung. Definiere einen einfachen, klaren Rahmen (Spielregeln) für diese Freiräume, an den sich alle halten müssen, auch das Leitungsteam.

Kinder und Jugendliche möchten schon früh für sich und andere Verantwortung übernehmen. Binde sie deshalb von Anfang an ein. Sie fühlen sich dadurch ernst genommen. Dies entbindet dich als Leiterperson keineswegs von deiner Verantwortung.

Beispiele aus der Praxis:
- Selbsteinschätzung bei Touren (evtl. mit Zusatzschlaufe oder Extra-Gipfelbesteigung): Lasse die Teilnehmenden mitentscheiden, auf welche Tour sie mitkommen oder ob eine Zusatzroute noch drin liegt.
- Vermeidung von Steinschlag in Geröllfeldern: Ein einfacher Gruppenwettbewerb ist, wer keine Steine lostritt. Reüssiert eine Gruppe, steigert dies das Verantwortungsgefühl jedes einzelnen.
- Kartenlesen bei einer Tour (evtl. Teilstrecken): Lasse die Teilnehmenden auf einem Etappenstück die Karte lesen.

Umgang mit Emotionen

Emotionen entstehen immer aus der Wahrnehmung einer bestimmten Situation, die Personen empfinden und bewerten. Während bei einer Person der Abstieg auf einem Felsgrat zu Freude führt, kann dieselbe Situation bei jemandem anders Angst auslösen.

Nimm die Emotionen der Teilnehmenden ernst und entwickle einen angemessenen Umgang damit.

Merkpunkte zu Angst

- Nicht jede Person, die Angst hat, sagt es auch.
- Angst kann sich auf verschiedene Art und Weise äussern: in der Mimik oder Körpersprache.
- Nimm Angst als normale (Warn-)Reaktion wahr. Angst blockiert, macht handlungsunfähig und kann zu einer eingeschränkten Aufmerksamkeit führen.
- Ergründe die Ursachen und behebe sie soweit als möglich. Verändere die Umstände soweit, dass ein Erfolg garantiert ist.
- Die erfolgreiche Überwindung der Angst ist auch eine Quelle positiver Emotionen: Freude, Befriedigung usw. Ebenso wird dadurch das Selbstvertrauen gestärkt.

Sind in deiner Gruppe schwächere oder ängstliche Teilnehmende dabei, so musst du sicherstellen, dass diese jederzeit auf die Unterstützung der Leitenden zählen können. Diese Teilnehmenden folgen deshalb bei anspruchsvollen Wegabschnitten unmittelbar hinter der Leiterperson.

Merkpunkte zu Freude

- Freude resultiert häufig aus der geglückten Auflösung gegensätzlicher Emotionen.
- Bei Lagersport/Trekking folgt oft auf die gemeinsame Entbehrung die Freude über die gemeinsame Leistung: Emotionen, die durch die Gruppe enorm verstärkt werden können.
- Freue dich als Leiterperson mit deiner Gruppe und koste solche Momente aus.
- Freude kann auch zu Übermut verleiten. Auf Bergwanderungen kann dies gefährlich sein.

Broschüre «Psyche – Theoretische Grundlagen und praktische Beispiele», Kapitel «Psyche regulieren»

Aktivitäten unterwegs

Sie bilden eine gute Ergänzung zum manchmal mühsamen und vielleicht langweiligen Wandern. Deshalb sollten vor allem vor und während Aufstiegen verschiedene Unterbrüche eingeplant werden.

Einige Kinder werden unterwegs Dinge entdecken und sind dementsprechend motiviert. Andere kommen an ihre Grenzen. Als Leiterperson unterstützt du sie, indem du mit ihnen spielst. Nimm dir auch Zeit, auf das einzugehen, was ihr unterwegs seht (Tiere, Pflanzen usw.). Informiere dich im Voraus über die Gegend. Dann kannst du den Kindern viel Spannendes erzählen (Geografisches, Sagen aus der Gegend, spezielle Gebäude usw.).

Spiele während des Wanderns

Tante von Marokko/Der Töff vom Polizischt/Vater Schlatter/usw.	**Ruf- und Singspiele**
Ein Fahrradsattel/En Huet, en Stock, en Rägeschirm/Vater Abraham/usw.	**Wanderspiele**
Wörterketten/«Ich packe in meinen Rucksack» (mit Dingen, die ihr unterwegs seht)/usw.	**Sprach- und Merkspiele**
Rückwärts-Geschichten/«Ich sehe eine Farbe, die du nicht siehst»/ Warm-Kalt/Blackstories/Stadt/Land/Fluss/usw.	**Rätsel und Fragespiele**
Möglichst viele unterschiedliche Blätter, Steine, Geräusche sammeln/Fotoausschnitte (die du beim Rekognoszieren gemacht hast) wiedererkennen/ usw.	**Aufgaben lösen**
Krokis in der Gruppe verteilen/Foto-OL/usw. Wegabschnitte mit Kartenteilen/Schatzsuche mit Hinweisen/usw.	**OL-Formen und Orientierungsspiele**
Geschichten erzählen, Schnitzeljagd (vordere Gruppe legt Spur).	**Diverses**

Mit zunehmendem Alter wird die Ausbildung unterwegs wichtiger. Mit Jugendlichen können Ausbildungsstopps durchgeführt werden, in denen du Wissen vermittelst. Die Jugendlichen können in der Gruppe diskutieren, nachdenken, auswerten oder etwas entscheiden. Wichtig ist, dass das Thema einen klaren Bezug zur aktuellen Situation hat. Es soll verständlich und konkret sein und den Jugendlichen nützlich erscheinen, um eine Situation zu bewältigen. Neben fachlichen Informationen soll die Gefühlsebene miteinbezogen werden: Greife dazu die aktuellen Emotionen der Teilnehmenden auf. Offene Fragen – Was? Wo? Warum? Wieso? Was-wäre-wenn? – helfen, eine Diskussion in Gang zu bringen und wecken die Neugierde.

PraxisTIPPS

- Plane genügend Zeit für die Ausbildungsstopps ein. Ernsthafte Ausbildungsstopps sollten zu grundsätzlichen Fragen und Diskussionen führen, was Zeit braucht.
- Wähle je nach Wetterverhältnissen einen regen- und windgeschützten Ort.
- Die Teilnehmenden sollen immer die Sonne im Rücken haben und nicht durch andere Aktivitäten in der Umgebung abgelenkt werden.
- Gib schon vor der Wanderung den Teilnehmenden Aufträge für Kurzbeiträge, Spiele oder Technikausbildungen im Gelände.

Ideen für Ausbildungsstopps

Kartenkunde
- Merkblatt «Orientierung».
- Handhabung Kompass/Kompassspiel.
- Lautes Kartenlesen/Vergleich von Kartenbild und Realität.
- Schätzen von Höhen und Distanzen.

Wetterkunde
- Merkblatt «Meteo».
- Wetterbeobachtungen/Wolkenarten/Vergleich Wetterbericht und Realität.
- Verhalten bei Gewitter und Blitz.

Diverses
- Gestein/Naturphänomene (Erosionserscheinungen, Schluchten, Gletscherränder, Geologie).
- Richtige Ernährung/Trinken bei Wanderungen.
- Natur- und Umweltschutz, Pflanzen bestimmen, Tiere beobachten, Spuren lesen.
- Notfallsituationen durchspielen (einüben).
- Strahlen (Kristalle suchen).

Orientierung

Richtiges Orientieren ist eine der wichtigsten Fähigkeiten eines Wanderleitenden. Denn es gibt wenig Mühsameres als mit einer ganzen Gruppe umkehren zu müssen, weil man einen falschen Weg genommen hat. Im Gebirge erhöht fehlerhafte Orientierung oft das Risiko, denn gerät man von der geplanten Route ab, kann das Gelände wesentlich anspruchsvoller werden. Auch das Umkehren wird oft schwieriger. Bist du an einer falschen Stelle abgestiegen und musst wieder hoch laufen, stehst du als Leiterperson plötzlich am Ende der Gruppe und nicht mehr an ihrer Spitze.

Hilfsmittel zur Orientierung

Neben natürlichen Wegweisern, die Hinweise über die Himmelsrichtungen geben (beispielsweise Moos an den Bäumen, Schneewächten, Sonne oder Polarstern), gibt es verschiedene Hilfsmittel, welche die Orientierung erleichtern.

Karte

Das zentrale Hilfsmittel zur Orientierung im Gelände ist die Karte. In den Schweizer Alpen haben wir den grossen Vorteil, dass flächendeckend sehr gutes Kartenmaterial besteht. Du kannst alle Blätter der Schweizer Landeskarten für J+S-Lager bei swisstopo ausleihen. Mache von diesem Angebot Gebrauch. Du kannst die Karten auch schon zum Rekognoszieren bestellen.

Höhenmesser

Ein Höhenmesser erleichtert in den Bergen die Orientierung bei schlechter Sicht. Alleine mit dem Höhenmesser kannst du jedoch deine Position nicht bestimmen. Er gibt dir nur die aktuelle Höhe und damit die Höhenkurve auf der Karte an, bei der du dich befindest. Oft hast du jedoch auf der Karte weitere Anhaltspunkte wie einen Weg, ein Felsband oder eine Rinne. Zusammen mit der Höhenangabe kannst du dann deine exakte Position bestimmen.

Ein barometrischer Höhenmesser misst den aktuellen Luftdruck und benutzt diesen um die aktuelle Höhe anzuzeigen. Da jedoch der Luftdruck auf einer bestimmten Höhe keine konstante Grösse ist, sondern von der Wetterlage abhängt, muss ein Höhenmesser zu Beginn einer Tour immer auf die aktuelle Höhe eingestellt werden. Vergisst du den Höhenmesser einzustellen, nützt er dir in einer schwierigen Situation nichts.

Neben barometrischen Höhenmessern können auch GPS-Geräte die Höhe anzeigen. Diese Höhenangabe ist jedoch wesentlich weniger genau. Die Genauigkeitsanzeige eines GPS-Gerätes bezieht sich nur auf die horizontale Position und nicht auf die Höhe.

Kompass

Im Gegensatz zum Höhenmesser hilft dir ein Kompass vor allem in flachem oder mässig steilem Gelände. Der Kompass hat zwei grundsätzliche Anwendungen. Erstens hilft er dir, die Karte richtig auszurichten und erleichtert es dir so, das Kartenbild ins Gelände zu übertragen. Hast du die Karte richtig ausgerichtet vor dir, ist die Orientierung einfacher und du benötigst weniger Zeit. Zweitens hilft der Kompass bei schlechter Sicht oder in unübersichtlichem Gelände, eine Richtung genau einzuhalten.

GPS

Ein GPS-Empfänger zeigt dir deine Position als Koordinate oder auf einer eingebauten Karte an. Die Position wird dabei mit Hilfe von Satelliten ermittelt. Zudem kann dir ein GPS-Gerät die Richtung und Distanz zu einem vorher bestimmten Punkt anzeigen (z. B. einer Hütte) oder die zurückgelegte Route aufzeichnen und damit den Rückweg erleichtern. Mit diesen Möglichkeiten ist ein GPS-Gerät neben der Karte das effektivste Hilfsmittel zur Orientierung.

Es hat jedoch zwei gravierende Nachteile. Erstens funktioniert es nur, wenn es Positionssignale von mindestens vier Satelliten empfangen kann. In den Alpen ist aber der Kontakt zu den Satelliten oft durch Berge eingestellt. Dadurch kann nicht immer eine Position angezeigt werden. Zweitens benötigt es Strom aus einer Batterie. Es kann deshalb auf längeren Touren nicht ständig eingeschaltet sein und bei Kälte entladen sich die Batterien schneller. Daher darfst du dich nie alleine auf das GPS-Gerät verlassen. Du weisst nicht, ob es nicht im entscheidenden Moment den Dienst versagt.

Orientierung erschwerende Faktoren

- Schlechtes Kartenmaterial (alt, ungenau, hoher Massstab, gar keine Karte).
- Schlechte Sicht, Nebel, Regen, Schneefall, Dunkelheit.
- Unübersichtliches Gelände, kein «Weitblick».
- Wegloses Gelände, schlechte Wegmarkierungen (oft in Gipfelnähe).

NORDA

NORDA ist eine Checkliste für die Kartenarbeit. Sie unterteilt das orientieren in fünf Schritte. NORDA eignet sich insbesondere für die Feinorientierung im Gelände von einem Punkt (z. B. Wegkreuzung, Gipfel, Pass) zum nächsten. Zu Beginn musst du also den Punkt bestimmen, den du als nächstes erreichen möchtest.

Auf der Webseite von J+S findest du ein Merkblatt, welches zu jedem Schritt geeignete Übungen enthält.

Nordrichtung

Die Karte nach dem Gelände oder mit dem Kompass nach Norden ausrichten. Nur die «genordete» Karte ist eine gute Hilfe. Wenn du auf das Norden verzichtest, machst du dir die Arbeit nur unnötig schwieriger.

Orientieren

Zuerst musst du deinen Standort auf der Karte bestimmen. Danach wird die Route zum nächsten Punkt geplant. Dabei entwickelst du aus der Karte eine Vorstellung, wie das Gelände bis zu diesem Punkt aussehen wird. Diese Vorstellung vergleichst du unterwegs mit der Realität. Zur Bestimmung deines Standorts kannst du umgekehrt vorgehen: Entwickle aus dem Gelände ein Modell und überlege, wie dieses auf der Karte aussieht. Suche den entsprechenden Ausschnitt auf der Karte.

Richtung

Um die geplante Richtung im Gelände einzuhalten, hilft die Methode «Kompass auf Karte». Die Karte bleibt mit Hilfe des Kompasses immer nach Norden ausgerichtet. So kannst du die Richtung aus der Karte bestimmen. Mit etwas Übung kannst du so ständig die Information aus der Karte mit der Kompassrichtung ergänzen. Bei schwierigen Verhältnissen wird die Richtung durch Peilen mit Hilfe des Kompasses gehalten.

Distanz

Überprüfe unterwegs immer, ob die zurückzulegende Distanz zum nächsten Orientierungspunkt schon überschritten ist. Diese kannst du mit Hilfe des Massstabs der Karte berechnen oder mit Hilfe der Koordinatenlinien (Abstand 1 km) aus der Karte schätzen. Daneben musst du dir ein Gefühl für die effektiv zurückgelegte Distanz aneignen. Vergleiche sie mit bekannten Distanzen wie einer 100-m-Bahn. Du kannst auch die Schritte zählen.

Auf oder ab?

Wie steil ist das Gelände? Muss ich zum nächsten Orientierungspunkt auf- oder absteigen? Die Hangneigung ergibt sich aus dem Abstand der Höhenkurven. Je enger diese beieinander liegen, desto steiler ist das Gelände.

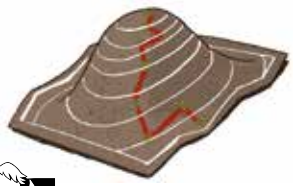

Broschüre «OL – Norda»

Orientierungsübungen

Orientierungslauf

Ein OL kann mit einer Wanderung kombiniert werden. Es müssen zum Beispiel Posten entlang der Route angelaufen werden. Je weiter die Posten vom Weg entfernt sind, desto schwieriger wird es. Mit einer vergrösserten Landeskarte kannst du in einer Region mit vielen Details auch in einem relativ kleinen Gebiet einen OL machen. Dadurch wird mehr Zeit für die Orientierung aufgewendet. Die reine Marschzeit wird kürzer.

Wichtig bei Orientierungsläufen ist, dass die Schwierigkeiten den Teilnehmenden angepasst wird. Sind die Teilnehmenden bei der Suche überfordert, führt dies zu Frustration. Sie lernen weniger. Setze die Posten an einem eindeutig identifizierbaren Objekt, das auf der Karte eingezeichnet ist. Andernfalls werden die Posten eher durch Zufall als durch Können gefunden.

Broschüre «Spiel und Sport», Kapitel «Orientierungslauf»

Kroki

Die Teilnehmenden zeichnen sich anhand der Karte ein Kroki zu einem Posten. Sie sind frei, welche Informationen sie in die Zeichnung aufnehmen wollen. Danach müssen sie nur mit ihrem Kroki den Posten finden.

Karte zu Gelände

Diese Übung eignet sich insbesondere für Pausen bei guter Sicht. Jemand wählt im Gelände einen Punkt aus (Haus, Gipfel, Pass). Alle versuchen, diesen Punkt auf der Karte zu finden. Danach wird die Übung in umgekehrter Richtung gemacht. Jemand bestimmt auf der Karte einen Punkt, und alle versuchen diesen Punkt im Gelände zu bestimmen.

Kompasslauf

Es wird ein Azimut und eine Distanz vorgegeben oder aus der Karte bestimmt. Dreiergruppen folgen möglichst genau der vorgegebenen Richtung. Die Übung kann als Gruppenwettbewerb organisiert werden (wer kommt dem Punkt am nächsten). Zur Steigerung der Schwierigkeit können auch mehrere Teilstrecken aneinandergehängt werden.

Übungen für schlechtes Wetter

Geländeprofile zu Höhenkurvenbild

Erstelle einige Zeichnungen von Geländeprofilen und dazugehörenden Höhenkurvenbildern. Die Teilnehmenden müssen die Höhenkurven jeweils dem richtigen Profil zuordnen. Die Übung kann auch als Memory gespielt werden.

Foto zu Kartenausschnitt

Erstelle einige Landschaftsfotos mit dazugehörigen Kartenausschnitten. Mit Satellitenbildern ist diese Aufgabe am einfachsten zu lösen. Mit Luftbildern wird sie schon schwieriger und mit am Boden aufgenommenen Fotos ist sie am anspruchsvollsten. Auch diese Übung kann als Memory gespielt werden.

Kartenpostenlauf

Es wird ein Startpunkt vorgegeben, von wo aus alle Teilnehmenden eine Route nachvollziehen müssen. Die Route wird unter anderem mit Azimuten, Distanzangaben, Höhendifferenzen beschrieben. Das Spiel kann auch als Wettbewerb organisiert werden.

Bergspezifische Gefahren

Es gibt so viele potentielle Gefahrenquellen in den Bergen, dass sie nicht abschliessend aufgezählt werden können. Es ist wichtig, immer aufmerksam zu sein und den gesunden Menschenverstand zu gebrauchen. Je mehr Erfahrung du hast, desto besser kannst du Gefahren erkennen.

Hast du eine Gefahr erkannt, muss die Verantwortung zur Reduktion des Risikos übernommen werden. Überlege dir im Voraus einfache und praktische Massnahmen, wie du das Risiko verringern kannst. Falls du unsicher bist oder das Risiko nicht auf ein vertretbares Mass reduzieren kannst, musst du auf die Durchführung verzichten. Doch auch bei guter Vorbereitung und grösstmöglicher Gefahrenprävention bleibt immer ein Restrisiko.

Absturz

Die häufigste Unfallursache beim Bergwandern ist der Absturz. Dieser wird meist durch ein Stolpern oder Ausrutschen ausgelöst. Wichtig ist, dass du beim Rekognoszieren potentielles Absturzgelände erkennst und dir überlegst, wie das Risiko minimiert werden kann.

Mögliche Massnahmen zur Vermeidung von Abstürzen:

- Vor Passagen, welche eine hohe Konzentration erfordern, eine kurze Pause machen.
- Klare Führung der Gruppe: Leiterpersonen zuvorderst und am Schluss der Gruppe, schwächste Teilnehmende gehen vorne in der Gruppe. Nahe beieinander bleiben.
- Konzentration auf den Weg, keine Ablenkungen.
- Stöcke bei engen Passagen oder falls die Hände gebraucht werden am Rucksack verstauen.
- Sind Hilfsmittel wie Metallseile oder -tritte vorhanden, diese auch nutzen.

Reichen diese oder ähnliche Massnahmen nicht aus und benötigst du zur Begehung einer Stelle alpine Sicherungsmittel (Seil, Anseilgurt), dann befindet sich deine Tour eindeutig nicht mehr im Bereich von LS/T.

Schneefelder

Auf Schneefeldern besteht oft Absturzgefahr. Im Sommer befinden sich Schneefelder meist in steilen, nordseitigen Rinnen oder Schattenhängen. Die Rutschgefahr ist morgens bei hartem Schnee wesentlich höher als nachmittags, wenn er bereits weich ist. Kannst du mit dem Schuh keinen Tritt schlagen und besteht gleichzeitig Absturzgefahr, darfst du die Passage nicht begehen.

Unter einem Schneefeld durchfliessende Bäche sind eine Gefahr, die oft schwierig zu erkennen ist. Oft besteht über dem Bach ein Hohlraum. Ist der Schnee weich oder die Schneeschicht dünn, droht ein Sturz durch die Schneedecke in den Bach. Am besten umgeht man solche Stellen oder stellt sicher, dass die Schneedecke genügend dick und stabil ist.

Auf Schneefeldern ist gutes Schuhwerk zentral. Mit Turnschuhen oder weichen Trekkingschuhen hat man zu wenig Halt und kann keine Tritte schlagen. Auch Wander- oder Skistöcke helfen gegen das Ausrutschen.

Es macht Spass beim Abstieg ein Schneefeld runter zu rutschen. Zudem gewinnst du Zeit. Achte aber immer darauf, dass ihr nur über Felder abrutscht, die flach auslaufen und bei denen kein Verletzungsrisiko besteht, sollte jemand nicht mehr selbst bremsen können.

Übungen zum sicheren Queren eines Schneefeldes (auf nicht zu steilem, flach auslaufendem Schneefeld üben):
- Schlag mit den Schuhen Tritte.
- Halte den Partner an der Hand und teste, ob ein Sturz gehalten werden kann.
- Slalom mit Skistöcken.
- Übt, auf das Kommando STOPP zu bremsen.
- Rutsche auf dem Rücken oder Hosenboden. Dreh dich zum Bremsen auf den Bauch und winkle Ellenbogen und Knie an.

Steinschlag

Steinschlaggefahr herrscht vor allem in steilen Geröllhalden, in steinigen Rinnen und direkt unterhalb von Felswänden.

Verhaltensregeln bei Steinschlaggefahr:
- Mach keine Pausen, halte dich möglichst kurz im gefährlichen Gebiet auf.
- Mach kleine Gruppen, die untereinander grossen Abstand halten. Es darf sich jeweils nur eine Gruppe im gefährdeten Gebiet befinden. Innerhalb der Gruppen läuft ihr aber dicht aufgeschlossen. Tretet sorgfältig auf und werft nie mutwillig Steine hinunter.
- Begehe kurze Geländepassagen, bei denen Steinschlag von weiter oben zu befürchten ist, einzeln.
- Bei Erwärmung nach einer Frostnacht, bei Regen oder nach einem Gewitter besteht erhöhte Gefahr.

Gewitter

Guten Schutz vor Gewittern bieten nur Gebäude mit Blitzableitern und Fahrzeuge. Alle anderen Orte, insbesondere auch Zelte, bieten nur minimalen bis gar keinen Schutz. Deshalb sollte man sich falls möglich während eines Gewitters in einem Gebäude oder einem Fahrzeug aufhalten.

Menschen werden selten direkt vom Blitz getroffen. Die grösste Gefahr bei Gewittern geht von den Spannungsunterschieden im Boden neben der Einschlagstelle aus. Die Gefahrenzone bildet einen Kreis rund 30 m um die Einschlagstelle.

Verhaltensregeln zur Vermeidung von Blitzschlag:

- Stimme die Tour auf Gewitteraktivität ab. Gewitter treten im Sommer meist am Nachmittag oder Abend auf. Bei Gewitterneigung muss die Tour rechtzeitig beendet werden.
- Suche spätestens bei Donner sichereres Gelände. Donner können über ca. 10 bis 15 km gehört werden. Falls kein sicherer Ort erreichbar ist, Gipfel und Grate meiden und möglichst auf der dem Gewitter abgeneigten Seite des Berges in tiefere Gebiete absteigen.
- Beachte Warnzeichen wie aufziehende Gewitterwolken oder schnell fallenden Luftdruck.
- Meide hohe Bäume, andere hohe Objekte und metallene Gegenstände. Falls möglich, suche eine Senke oder Rinne auf.
- Stelle die Füsse möglichst nahe zusammen, gehe in die Hocke und halte die Arme am Körper, um die Schrittspannung zu minimieren. Lege dich auf keinen Fall auf den Boden und lehne dich nie an eine Felswand.

Glücklicherweise sind Todesfälle durch Blitzschlag im Vergleich zu allen anderen Bergunfällen selten.

Nebel und Schneefall

Nebel und Schneefall verringern die Sicht und erschweren dadurch die Orientierung. Zudem können Kälte und Nässe zu einer Gefahr werden. Bei Schneefall kommt oft auch noch Nebel hinzu. Eine relativ einfache Wanderung kann so wesentlich anspruchsvoller oder gar undurchführbar werden. Es ist deshalb wichtig, sich bereits bei der Planung zu entscheiden, ob eine Wanderung auch bei Nebel oder Schneefall durchgeführt werden kann. Mit Schneefall muss insbesondere im Frühling oder Herbst ab 1000 m ü. M. gerechnet werden. In den Alpen kann es aber auch im Sommer schneien.

Weitere Hinweise zur Orientierung unter erschwerten Bedingungen findest du im Kapitel Orientierung.

Ernährung

Hunger und Durst sind lästige Begleiter auf einer Wanderung. Sie nagen an den Energiereserven und können eine Tour zur Tortur machen. Eine falsche Ernährung führt zu vorzeitiger Ermüdung. Wenn du frühzeitig auf deinen Körper hörst und die Energiereserven mit einer Zwischenmahlzeit auflädst, stehen die Chancen besser, dass die Wanderung gelingt. Für ein Zelttrekking musst du besonders umsichtig einkaufen, denn du trägst die Lebensmittel mit und musst sie vielleicht unter erschwerten Bedingungen zubereiten. Beim Wandern wird viel Energie verbraucht, was du in der Menüplanung berücksichtigen musst. Andere Faktoren für die Mengenbestimmung sind die Höhe, Temperatur (Wärme, Kälte) und das Wetter (Regen, Wind).

Menüplanung und Einkaufen

Bei der Planung des Menüs musst du einige Punkte beachten. Neben einer ausgewogenen Ernährung, die alle erwähnten Nährstoffe enthält, muss das Essen auch schmecken. Ausreichend Kohlenhydrate gewährleisten, dass auch am nächsten Tag noch genügend Energie vorhanden ist.

- Kosten: Die Verpflegung für eine Unternehmung kostet deutlich mehr als in einem gewöhnlichen Lager.
- Haltbarkeit: Verwende lange und ungekühlt haltbare Lebensmittel. Verzichte auf verderbliche Frischprodukte. Nimm Trocken- und Pulvernahrung, die mit Wasser aufgekocht werden kann.
- Verpackung: Diese sollte möglichst klein und leicht sein. Verzichte auf Büchsen oder Glasflaschen. Fülle Lebensmittel aus voluminösen Verpackungen in Plastiksäcke oder kleine Kunststoffbehälter um. Dies verringert auch den Abfall.
- Wassergehalt: Gemüse, Früchte und andere Lebensmittel mit hohem Wassergehalt kommen wegen ihrer Grösse und ihres Gewichts auf mehrtägigen Trekkings eher selten zum Einsatz. An ihrer Stelle finden dafür Dörrfrüchte im Rucksack Platz.
- Kochzeit: Wähle Menüs mit einer raschen Kochzeit, dies verringert den Brennstoffverbrauch. Unterwegs auf dem Feuer oder Kocher dauert alles ein bisschen länger.
- Pfannen: Koche einfache Menüs, die nur wenige Pfannen benötigen. Das spart Platz und Gewicht.

Ernährung vor, während und nach der Tour

In Ruhe ein reichhaltiges, nicht zu üppiges Morgenessen mit einem warmen Getränk zu geniessen, weckt die Lebensgeister und regt den Organismus an. Iss genügend Kohlenhydrate, damit du während der Tour nicht gleich ins Energieloch fällst.

Nimm in jeder Pause, aber mindestens alle zwei Stunden, etwas zu dir. Primär sind Kohlenhydrate und Proteine geeignet. Ermuntere Gruppenmitglieder, die ihre Leistungsgrenze erreicht haben und keinen Hunger haben, dazu, etwas zu essen. Ohne Nahrungszufuhr sinkt der Blutzuckerspiegel und die Leistungsfähigkeit nimmt rasch ab.

Mit dem Nachtessen kompensierst du das Kalorien- und Flüssigkeitsdefizit und füllst die Kohlenhydratdepots in den Muskeln wieder auf. Koche auch bei widrigen Witterungsbedingungen eine warme Mahlzeit. Eine Bouillon als Vorspeise gleicht den Salzverlust des Körpers durch das Schwitzen aus.

Nach Ankunft von einer anstrengenden Etappe kann die Erholung wesentlich verkürzt werden: Konsumiere in den ersten 15–30 Minuten eine Bouillon oder ein kohlenhydratreiches Getränk und führe dem Körper möglichst viele Kohlenhydrate zu (z. B. Teigwaren, Brot). Erschöpfte, die nur noch schlafen möchten, müssen unbedingt essen.

Ernährungsgrundlagen
Unsere Nahrung enthält verschiedene Nährstoffe, die dem Körper die Energie für die körperliche Aktivität liefern.

Kohlenhydrate
Kohlenhydrate kommen in Gemüse, Getreide, Früchten, Süssigkeiten oder Sportgetränken vor. Sie sind die wichtigsten Energielieferanten, und diese Energie kann der Körper sehr schnell gut nutzen.

Fette
Fette sind wichtige Reservestoffe, um den hohen Energieverbrauch auf Wanderungen überhaupt decken zu können. Auf längeren Touren wird die Energie sogar hauptsächlich aus dem Fettstoffwechsel bezogen. Fette sind in Butter, Öl, Nüssen, Käse und Wurstwaren enthalten.

Proteine
Proteine oder Eiweisse sind Baustoffe für die Körperzellen. Sie sind beim Aufbau der Muskulatur wichtig oder tragen zu einer verbesserten Konzentrationsfähigkeit bei. Proteine kommen in Milch und Milchprodukten, Fleisch, Fisch, Eiern, Tofu, Nüssen und Getreide vor.

Anzeichen eines Flüssigkeitsmangels: Leistungsminderung, Schwindel, Kopfschmerzen. Bei erhöhten Verlusten begleitet von Müdigkeit, Erschöpfung, Übelkeit, Kraft- und Appetitlosigkeit.

Getränke

Während einer sportlichen Betätigung wird der Körper stark erwärmt. Das Schwitzen hilft dem Körper sich abzukühlen. Im Durchschnitt gehen über Haut, Atmung, Darm, Urin und Schweiss etwa 2,5 l Wasser pro Tag verloren. Dieses muss ersetzt werden. Bei Ausdauerleistungen wie Wandern ist die Flüssigkeitszufuhr deshalb sehr wichtig. Du solltest regelmässig kleine Portionen eines gut verträglichen Getränks zu dir nehmen. Vertraue aber nicht auf dein Durstgefühl. Bei grosser Anstrengung nimmt es nicht in dem Ausmasse zu, wie es dem tatsächlichen Wasserverlust entspricht. Trinke darum vor dem Durst, weil es deine Leistung verbessert! Auf einer Tour definiert die Trinkflasche die Flüssigkeitsmenge, die du aufnehmen kannst. Ein Trinksystem (Wasserbehälter mit Trinkschlauch) mit in der Regel grösserem Volumen kann hier Abhilfe schaffen. Es verleitet aber zu Beginn einer Tour häufig zu unkontrolliertem Trinken, was gegen Ende der Wanderung zu Engpässen führen kann. Decke den Flüssigkeitsbedarf deshalb vor allem morgens und abends.

Die Kinder und Jugendlichen auf einer Tour sollen trinken, was sie gerne haben.

Ausrüstung

Die Ausrüstung für eine Wanderung unterscheidet sich je nach geplanter Route und Verhältnissen. Für einfache Tagestouren benötigst du weniger Material als für eine Tour mit Biwak. Einer der grössten Vorbehalte, ein Bergtrekking mit dem Zelt oder eine Wanderung mit Biwak durchzuführen, ist der schwere Rucksack. Umso wichtiger ist es, alles Unnötige zu Hause zu lassen, ganz nach dem Motto «So wenig wie möglich – so viel wie nötig». Je leichter das Gepäck, umso grösser die Leistungsfähigkeit der Teilnehmenden.

Führst du eine Wanderung mit Kindern durch, hast du vielleicht Kinder dabei, die noch nicht oft oder noch gar nie gewandert sind. Darum ist es wichtig, dass du den Eltern vor der Wanderung Ausrüstungs-Empfehlungen bekannt gibst. Dies erhöht die Sicherheit der Kinder und kann dir bei der Durchführung vieles erleichtern.

Eine vollständige Packliste für ein Bergtrekking oder eine Wanderung findest du auf dem Merkblatt «3 × 3 – Unterwegs sein».

Merkblatt «Lagersport/Trekking – 3 × 3 unterwegs sein»

Bekleidung

Die Ideale Bekleidung für eine Unternehmung besteht aus mehreren Schichten. In dieser Kombination hat jede Schicht ihre Funktion:

1. Schicht: Diese liegt direkt auf der Haut und muss in erster Linie den Schweiss von der Haut wegführen. So bleibt diese trocken und man friert nicht. Gut geeignet für diese Schicht ist synthetische Unterwäsche oder Merinowolle.
2. Schicht: Diese soll den Schweiss von der ersten Schicht übernehmen, diesen wenn möglich weiterleiten und vor allem den Körper warm halten. Beispiele: Faserpelzpullover Windstopper, Soft-Shell.
3. Schicht: Diese ist der Schutz gegen Wasser, Wind, Sonne und mechanische Beanspruchung. Sie soll die Feuchtigkeit möglichst gut nach aussen abgeben, weshalb die Atmungsaktivität besonders wichtig ist. Beispiele: Jacke aus semipermeablen Membranen, einem Gewebe oder mit einer Beschichtung.

Synthetik oder Baumwolle? Diese Frage beschäftigt die Outdoorsportler schon lange.

	Baumwolle	Merinowolle	Synthetik
Vorteile	Kostengünstig Angenehm zu tragen	Sehr leicht Geruchsarm Kühlt bei warmen Temperaturen, Wärmt bei kalten Temperaturen. Atmungsaktiv	Isolierend auch im feuchten Zustand Schnell trocknend Atmungsaktiv
Nachteile	Grosse Feuchtigkeitsaufnahme Trocknet sehr langsam	Teuer	Geruchsempfindlich (Schweiss)

Schuhe

Wichtigste Voraussetzung für ein möglichst beschwerdefreies Marschieren sind gut eingelaufene Schuhe. Der Schuh sitzt dann richtig, wenn du nach sattem Schnüren auf eine abfallende Ebene stehst und deine Zehen den Schuh vorne nur ganz leicht berühren. Die folgende Übersicht gibt dir Anhaltspunkte zu den verschiedenen Schuhtypen.

Trekkingschuhe

Trekkingschuhe bieten viel Gehkomfort. Sie besitzen eine weiche und leichte Profilsohle. Sie bieten im einfachen Gelände ausreichend Halt. Die Höhe des Schaftes variiert, geht meist jedoch nur bis zum Knöchel. Beim Obermaterial kommen meistens atmungsaktive und wasserresistente Membranen zum Einsatz.

Wanderschuhe

Wanderschuhe bieten Gehkomfort und Schutz gegen das Umknicken des Fussgelenks. Sie besitzen eine feste Profilsohle und einen hohen Schaft. Meist besteht das Obermaterial aus einer Membran, manchmal auch aus Leder. Während Membranen atmungsaktiv und dauerhaft wasserresistent sind, bietet Leder einen höheren Tragkomfort.

Bergschuhe

Bergschuhe kommen in anspruchsvollem Gelände zum Einsatz. Sie haben eine steife Sohle mit rutschfestem Profil und sind wasserresistent. Ein hoher, fester Schaft verhindert das Umknicken des Fussgelenks. Das Obermaterial besteht entweder aus einer Membran oder aus Leder.

Damit die Schuhe ihre Wasserresistenz behalten und lange halten, braucht das Obermaterial eine regelmässige Pflege. Zur Vermeidung von Blasen kommt neben gut passenden Schuhen auch den Socken eine wichtige Funktion zu: Diese sollten eine gute Passform aufweisen und je nach Einsatzgebiet ausreichend gepolstert sein (z. B. im Bereich des Schienbeins).

Kontrolliere vor Wanderungen – noch besser sogar vor dem Lager – die Schuhe der Teilnehmenden: Haben sie genug Profil und geben sie genügend Halt für die geplante Wanderung? Sind sie imprägniert? Damit kannst du dir unangenehme Überraschungen während der Wanderung ersparen.

Rucksack

Nur mit einem guten Rucksack lässt sich viel Material bequem tragen. Er sollte den Rücken und die Schulterpartien optimal entlasten und das Gewicht dank eines breiten Hüftgurts auf die Hüfte verteilen, ohne dabei die Bewegungsfreiheit einzuschränken. Die Hüfte sollte etwa 50–75 % des Gewichtes tragen.

Empfohlene Grössen für eine Aktivität
- Längere Trekkingtour: 50–70 l.
- Wochenendtour: 30–50 l.
- Tagestour: 10–30 l.

Empfohlenes Traggewicht für Kinder/Jugendliche
- Tag/Wochenendtour: 15–20 % des Körpergewichts.
- Längere Touren: 10–15 kg.

Kochausrüstung

Das Kochen auf Unternehmungen stellt erhöhte Anforderungen an die Kochequipe. Auf Wanderungen unterhalb der Baumgrenze kann gut über dem Feuer gekocht werden, oberhalb der Baumgrenze jedoch muss mit Gas-, Benzin-, oder Spirituskochern gekocht werden. In beiden Fällen muss das dafür notwendige Material ständig mitgetragen werden, was sich in Volumen und Gewicht bemerkbar macht.

	Kochen über dem Feuer	Gaskocher	Benzinkocher	Spirituskocher
Prinzip	Mit gesammeltem oder mitgebrachtem Holz ein Feuer entfachen und Kochtöpfe darüber hängen (z. B. mit einem Dreibein).	Gaskartusche an den Kocher anschliessen, Ventil öffnen und anzünden.	Brennstoffflasche an den Kocher anschliessen und mit der Pumpe Druck in der Flasche aufbauen. Der flüssige Brennstoff wird nicht direkt verbrannt, sondern seine Gase. Deshalb muss der Kocher vorgewärmt werden.	Bei dieser Kocherart existieren verschiedene Systeme. Der Brennstoff wird dabei gasförmig verbrannt. Je nach System muss der Brenner zuerst vorgeheizt werden.
Vorteile	Brennstoff kann vor Ort gesammelt werden. Kostenlos.	Einfach in der Anwendung. Leicht und präzise in der Regulierung der Flamme. Verbrennen den Brennstoff ohne zu russen. Gaskartuschen sind durch ihre Verschlusssysteme sicher.	Ausgezeichnete Heizleistung. Temperaturresistenz. Einfache Brennstoffbeschaffung.	Einfach und sauber in der Anwendung. Wartungsarm. Sicher.
Nachteile	Schwierigkeiten je nach Wetter (Wind, Regen). Feuerverbote in gewissen Regionen/bei gewissen Wetterlagen.	Bei Kälte reduzierte Leistung. Beschaffung von passenden Gaskartuschen.	Manchmal unerwartete Stichflammen beim Vorheizen. Regelmässige Wartung und Reinigung wegen des Russes nötig.	Sehr beschränkte Heizleistung. Die Flamme des Brenners lässt sich kaum regulieren. Bei Kälte funktionieren sie nur eingeschränkt.

Ein guter Wind- und Wärmeabstrahlungsschutz (z. B. aus faltbarem Aluminium), der um den Kocher gestellt wird, vermindert die Kochzeit.

Alle Kochertypen weisen eine nicht zu unterschätzende Gefahr auf: Sie benötigen entflammbares Material und können – wenn gedankenlos bedient – schwere Verletzungen verursachen. Das Verschütten von Benzin, das Berühren eines heissen Tanks oder das Wechseln von Gaskartuschen bei defekten Dichtungen kann zu gefährlichen Explosionen führen. Koche nie im Zelt (Dämpfe, Stichflammen). Der Umgang mit dem Kocher muss vor der Unternehmung geübt werden. Alle Brennstoffe müssen in speziell dafür geeigneten, widerstandsfähigen, nicht verwechselbaren Behältern mit sicheren Dichtungen transportiert werden.

Pfannen

Die Anzahl und Grösse der Pfannen, die auf eine Unternehmung mitgenommen werden, hängt einerseits von der Gruppengrösse und andererseits vom geplanten Menü ab. Im Handel finden sich Töpfe von einem Liter Inhalt bis zu 3,5 Litern bzw. 14 Litern bei den Pfadikesseln. Häufig bestehen die Töpfe aus Aluminium, da dies sehr leicht ist und eine hervorragende Wärmeleitfähigkeit besitzt. Sie sind auch günstig. Alu ist ein weiches Metall, weshalb die Pfannen jedoch rasch Kratzer oder Dellen kriegen. Alternativ gibt es Pfannen, welche aus hartanodisiertem oder harteloxiertem Aluminium bestehen. Diese sind kratzfest und langlebiger. Sie weisen innen meist eine Antihaft-Beschichtung auf. Edelstahl ist ein weiteres Material, das häufig für Pfannen verwendet wird. Es ist relativ schwer, dafür aber robust, rostfrei und hat eine akzeptable Wärmeleitfähigkeit.

Schlafsack und Isoliermatten

Gute Daunenschlafsäcke haben ein geringes Gewicht, ein speziell kleines Packmass und geben sehr warm. Sie eignen sich deshalb gut für Unternehmungen und Trekkings. Synthetische Schlafsäcke behalten zwar in feuchtem Zustand ihre Isolationsfähigkeit besser als Daunen, sind dafür wesentlich weniger komprimierbar und schwerer. Beim Zelttrekking ist die Wahrscheinlichkeit gross, dass der Schlafsack zumindest feucht wird (Kondenswasser im Zelt, Tau); er sollte deshalb vor dem Verpacken nach Möglichkeit getrocknet werden.

Die Wärmeleistung eines Schlafsacks ist von den äusseren Bedingungen wie Bodentemperatur, Wind, Feuchtigkeit und Aussentemperatur abhängig. Aber auch persönliche Empfindungen oder der psychische Zustand des Benutzers beeinflussen den «Komfortbereich» eines Schlafsacks. Für ein Bergtrekking eignen sich Schlafsäcke, die zumindest die Bezeichnung «Drei-Jahreszeiten-Schlafsack» aufweisen.

Für kurze Unternehmungen mit Biwak reicht eine einfache Schaumstoffmatte. Bei einem Bergtrekking mit Zeltübernachtung oder Biwak ist eine gute Unterlagsmatte jedoch sehr zu empfehlen. Sie muss den Wärmeaustausch zwischen dem warmen Körper und dem kalten Boden verhindern. Leichte und kompakte aufblasbare Matten haben sich bewährt. Sie bieten auch einen gewissen Liegekomfort. Einige Matten sind zusätzlich mit Daunen oder Kunstfasern gefüllt, was die Luftzirkulation dämmt und so für einen besseren Isolationswert sorgt.

Zelte und Biwak mit Blachen

Für eine kurze Unternehmung mit Biwak werden nicht zwingend Zelte benötigt. Du kannst auch ein Blachenzelt mit J+S-Leihmaterial bauen. Sind genügend Teilnehmende dabei, kann das anfallende Gewicht gut verteilt werden. Für ein mehrtägiges Trekking in den Bergen haben sich Leichtgewichts-Tunnel- oder -Kuppelzelte bewährt. Diese sind so klein und leicht, dass sie von einer Person getragen werden können und Platz für mindestens zwei Personen bieten. Sie bieten je nach Modell auch auf einer oder beiden Seiten Platz, um z. B. den Rucksack deponieren zu können. Es werden zwei Typen von Zelten für Trekkings unterschieden:

Tunnelzelte: Sie bieten das beste Verhältnis von Grundfläche zu Raumvolumen und das geringste Gewicht pro Schlafplatz. Sie sind rasch aufgebaut, können jedoch nicht ohne Heringe frei stehen. Die Längsseite muss parallel zum Wind aufgestellt werden.

Kuppelzelte: Sie sind selbststehend (ohne Heringe) und widerstandsfähiger gegen Belastungen durch Wind oder Schnee als Tunnelzelte. Ihr Innenraum ist im Verhältnis zur Grundfläche aber kleiner. Bei einigen Zelten kann das Innenzelt auch ohne Aussenzelt aufgestellt werden. Dies ist in besonders warmen Nächten praktisch.

Für solche Zelte werden leichte und dünne Stoffe verwendet. Deshalb sollte am Boden eine passende Zeltunterlage verwendet werden, damit keine Risse im Zelt entstehen, wenn der Boden mal nicht ganz eben oder steinfrei ist.

Willst du für eine zweitägige Tour etwas Gewicht sparen, aber trotzdem nicht auf das Erlebnis des draussen Übernachtens verzichten, kannst du auch unter freiem Himmel schlafen. Für solche Übernachtungen oberhalb der Baumgrenze braucht es unbedingt einen wasserdichten und dampfdurchlässigen Biwaksack. In den Bergen wird es insbesondere in klaren Nächten kalt und wegen des Taus auch ohne Regen feucht. Biwakübernachtungen ohne Zelt sollten nur bei sicherer Schönwetterlage durchgeführt werden. Falls das Wetter unsicher ist, nimmst du besser ein Zelt mit, organisierst eine Notunterkunft oder verzichtest auf die Tour.

Übernachtung

Dem richtigen Ort zum Übernachten kommt eine wichtige Rolle zu. Einerseits hilft eine ruhige Nacht bei der Erholung nach der Wanderung. Andererseits bleiben attraktive Übernachtungsplätze vielen Teilnehmenden nachhaltig in Erinnerung.

Biwakieren

Biwaktouren bieten unvergessliche, abenteuerliche Erlebnisse. Durch das ständige Draussenleben nimmst du die Natur viel intensiver wahr. Du bist aber den Naturgewalten jederzeit ausgesetzt. Dadurch ist reines Zelttrekking die anspruchsvollste Unternehmungsform in Lagersport/Trekking. Ein Biwak eignet sich primär für Jugendliche.

Kriterien für einen geeigneten Biwakplatz:
- Ausserhalb von Schutzgebieten.
- Möglichst flach und eben, meide Mulden (Wasseransammlung).
- Nicht an exponierter Lage (Berggrat, Gipfel, steinschlaggefährdete Hänge).
- Windgeschützte Lage.
- Keine Überschwemmungsgefahr: Bei starkem Regen können sich kleine Bächlein in Berggebieten innert kurzer Zeit in reissende Flüsse verwandeln.
- Lasse genügend Raum, damit du nicht über die Zeltschnüre des Nachbarzeltes stolperst.
- Keine Absturzgefahr in unmittelbarer Nähe (beachte Dunkelheit).
- Trinkwasser in der Nähe (Quelle, Bach, evtl. Schneefeld).
- Keine weidenden Tiere in der Nähe, Absperrung zur Weide.
- Mögliche Notunterkunft in der Nähe.

Beachte bei der Planung einer Biwaktour die Weisungen für den Sicherheitsbereich «Berg».

Informiere dich über Wildschutzgebiete und Wildruhezonen in der vorgesehenen Region. In allen eidgenössischen Jagdbanngebieten und in den meisten kantonalen und kommunalen Schutzgebieten ist das Biwakieren verboten. Alle eidgenössischen Jagdbanngebiete findest du online unter http://map.bafu.admin.ch. Weitere Schutzgebiete sind unter http://www.wildruhezonen.ch/ abrufbar. Dort erfährst du auch, welche Regelungen in den Schutzgebieten in welchen Zeiträumen gelten. Um sicher zu gehen, informiere dich bei der lokalen Gemeindeverwaltung. Diese kann dich an die zuständige Person weiterleiten (Förster, Jagdinspektor, Grundeigentümer).

http://map.bafu.admin.ch
www.wildruhezonen.ch

Hüttenübernachtung

Bei Übernachtungen in Berghütten kann auf das Mittragen von Zelten, Schlafsäcken, Kochutensilien und allenfalls sogar Esswaren verzichtet werden. Du kannst die Etappenlänge und Marschzeit entsprechend verlängern, da ein beträchtlicher Teil der Last wegfällt. In bewarteten SAC-Hütten und etlichen Privathütten wird Halbpension mit Übernachtung, Frühstück und Nachtessen angeboten. Du kannst in einigen Hütten das Essen auch selbst mitbringen. Möglicherweise musst du aber eine Gebühr bezahlen. Auf jeden Fall musst du dies vorgängig mit dem Hüttenwart absprechen. In einigen Hütten gibt es Spezialtarife für J+S-Gruppen.

Ein Verzeichnis aller SAC-Hütten und die genauen Reservationsbedingungen findest du unter www.sac-cas.ch. Hinweise auf weitere Hütten sind in Wanderführern oder auf der Landeskarte vermerkt (Symbol «Abgelegener Gasthof»).

www.sac-cas.ch

Bergrettung

Unfälle und Erkrankungen in den Bergen stellen für die Beteiligten eine besondere Herausforderung dar und können rasch zu einer Stresssituation werden. Nicht nur, dass sie meist weit weg vom nächsten Arzt oder Spital geschehen, sondern weil auch Umweltfaktoren wie das Wetter sich erschwerend auf die Situationsbewältigung auswirken können. Auch auf vermeintlich einfachen Wanderungen im Flachland können Unfälle geschehen. Das grundsätzliche Vorgehen richtet sich auch hier nach den im Folgenden beschriebenen Abläufen.

Vorgehen im Notfall

Um in Notfallsituationen richtig und rasch handeln zu können, sind Merksätze und festgelegte Abläufe hilfreich.

Als erstes gilt folgender Grundsatz:
Schauen – Denken – Handeln

Schauen

Hier verschaffst du dir einen Überblick, was genau geschehen ist.
- Wie viele Personen sind betroffen?
- Wie schwer sind deren Verletzungen?
- Wie viele Personen hast du zur Unterstützung?

Ganz wichtig ist es auch abzuklären, ob an der betroffenen Unfallstelle objektive Gefahren wie Absturzgefahr oder Steinschlag bestehen, sowohl für die Verletzten wie auch die Unverletzten.

Denken

Nachdem du die Situation überblickt hast, legst du dir eine Handlungsstrategie zurecht. Dabei werden die allenfalls vorhandenen Gefahren, die Anzahl der Verletzten und die Art der Verletzung berücksichtigt. Wenn du noch andere Leiterinnen und Leiter dabei hast, die dich unterstützen können, so überlege dir auch, wem du welche Aufgabe delegieren kannst. Die Führung bei der Ereignisbewältigung muss jedoch immer bei einer Person bleiben.

Handeln

Hast du dir deine Strategie überlegt, dann wird die Situation möglichst zielgerichtet bewältigt. Dabei steht der Schutz vor objektiven Gefahren an und das Leisten von Erster Hilfe. Vergiss auch nicht, dass sich eine Leiterperson den unverletzten Teilnehmenden widmet. Wichtig ist, dass man sich und die anderen Teilnehmenden nicht durch überstürztes Vorgehen gefährdet.

Als zweites gilt folgender Grundsatz:
Alarmieren – Sichern – Bergen – Erste Hilfe

Alarmieren
In den Alpen kann auch an abgelegenen Orten in relativ kurzer Zeit professionelle Hilfe von aussen angefordert werden. Es lohnt sich, die Alarmierung früh durchzuführen, denn durch eine verspätete oder vergessene Alarmierung geht wertvolle Zeit verloren. Sind mehrere Leitende vor Ort, kann das Alarmieren auch an eine Person delegiert werden. Als Gedankenstütze und damit bei der Alarmierung nichts vergessen geht, helfen dir die Merkpunkte beim Alarmierungsauftrag auf dem J+S-Notfallblatt. Als Alarmierungsmittel kommen zum einen Mobiltlefone in Frage, welche mittlerweile auch in den Alpen ziemlich guten Empfang haben. Ist nur ein fremdes Netz verfügbar, kann die internationale Notrufnummer 112 trotzdem angerufen werden. Zum anderen helfen Funkgeräte mit dem Emergency-Kanal, über welchen direkt die Einsatzzentrale der Rega erreicht werden kann.

PraxisTIPP

Hast du auf deinem Smartphone die Rega-App installiert, kannst du im Notfall damit alarmieren. Die Rega erhält dann zusätzlich per SMS die Koordinaten deines aktuellen Standortes.

Hast du am aktuellen Standort weder mit dem Mobiltelefon noch einem Funkgerät Empfang, muss umgehend der Standort gewechselt werden. Dazu geht man am besten zum letzten bekannten Standort mit Empfang zurück oder steigt zu einer höher gelegene Position, von der aus man freie Sicht hat. Es lohnt sich, Empfangslücken beim Rekognoszieren auf der Karte zu markieren, um später sofort zu wissen, wo die nächste Position mit Empfang ist.

Sichern
Eine Gefährdung von dir, deinen Helfern und den weiteren Personen vor Ort muss möglichst vermieden werden. Deshalb ist der Schutz vor Absturz und Steinschlag zentral. Erst dann wird der oder die Verletzte geschützt.

Bergen
Um Verletzte vor weiteren Gefahren zu schützen, müssen sie oft geborgen werden. Dabei gilt es zu beachten, dass dadurch keine zusätzlichen Verletzungen verursacht werden. Je nach Situation müssen manchmal auch Kompromisse eingegangen werden.

Erste Hilfe
Wenn der oder die Verletzte vor weiteren Gefahren geschützt ist, wird mit der Ersten Hilfe begonnen.

Ablauf der Ersten Hilfe

http://www.resuscitation.ch

Die Erste-Hilfe-Massnahmen richten sich nach der Art und Schwere der Verletzung. Allgemein kannst du dich an den folgenden Ablauf halten:

1. Lebensrettende Sofortmassnahmen gemäss aktuellem Schema.
2. Body Check.
3. Erweiterte Erste-Hilfe-Massnahmen.
4. Lagerung und Überwachung.

Mit den lebensrettenden Sofortmassnahmen erreichst du, dass die verletzte Person weiterhin mit Sauerstoff versorgt wird und sich keine weiteren Schäden ergeben. Beim anschliessenden Body Check geht es um eine Ganzkörperuntersuchung mit dem Ziel, keine Verletzung, die behandelt werden muss, zu verpassen. Du achtest dabei speziell auf Blutungen, Schwellungen, Verhärtungen, Fehlstellungen und andere schmerzhafte Stellen.

Bei den erweiterten Erste-Hilfe-Massnahmen werden allenfalls Verbände angelegt, verletzte Körperteile ruhig gestellt (fixiert) und Vorbereitungen für Lagerung und Transport getroffen.

Die Lagerung ermöglicht dem Verletzten ein möglichst bequemes Warten auf weitere medizinische Hilfe. Sie verbessert die Situation und vermeidet zusätzliche Gefährdungen. Mit der anschliessenden Überwachung erreichst du, dass du Situationsveränderungen bei der verletzten Person sofort bemerkst. Um den Zustand des Verletzten festzuhalten, füllst du das Patientenprotokoll im J+S-Notfallblatt aus. Dieses kannst du dem behandelnden Arzt mitgeben.

Sinnvollerweise übst du verschiedene Erste-Hilfe-Massnahmen bereits im Vorfeld, da es wichtig ist, in Stresssituationen auf vorhandenes Wissen zurückgreifen zu können. Dazu bieten Besuche eines Erste-Hilfe- oder Samariterkurses und entsprechende Wiederholungskurse praktische Gelegenheiten.

Ausrüstung

Damit du für Notfälle auf Wanderungen gerüstet bist, musst du die entsprechende Ausrüstung mitnehmen. Dazu gehört eine Apotheke, Kommunikationsmittel wie Mobiltelefon und/oder Funk, das J+S-Notfallblatt und, falls du länger mit einer Gruppe unterwegs bist, ein kleines Buch zum Nachschlagen, was bei speziellen Erkrankungen oder Verletzungen zu tun ist.

In der Apotheke solltest du nur das mitnehmen, was du anwenden kannst und darfst. Neben allgemeinem Verbandsmaterial, das in einer handelsüblichen Notfallapotheke vorhanden ist, sollte auf eine Wanderung das Folgende mitgenommen werden:

- Rettungsdecke.
- Einweghandschuhe.
- Elastische Binde.
- Formbare Polsterschiene.
- Tape.
- Zwei verschiedene Schmerzmittel mit unterschiedlichen Wirkstoffen (aufgrund möglicher Unverträglichkeiten und unterschiedlicher Wirkung).

Transport

Der Transport von verletzten Personen kann sich in den Bergen als schwierig erweisen. Meist steht keine Zufahrtsstrasse zur Verfügung, so dass nur eine Helikopterrettung in Frage kommt. Der Helikopter benötigt einen Landeplatz, der folgende Anforderungen erfüllt:

- Horizontale, ebene Aufsetzfläche von 6 × 6 m.
- Hindernisfreie Zone von 25 × 25 m.

Weise bei der Alarmierung die Einsatzzentrale auf allfällige Flughindernisse in deiner Umgebung hin. Erwähne ebenso, wenn das Gelände spezielle Anforderungen an die Rettung stellt, die zum Beispiel die Seilwinde oder einen Rettungsspezialisten- Helikopter (kurz: RSH) erfordern. Diese werden immer dann zugezogen, wenn gebirgstechnische Erfahrung oder Unterstützung für Bergungsarbeiten erforderlich sind.

J+S-Notfallblatt, Helikopterrettung

Kann der Helikopter aufgrund von schlechtem Wetter nicht fliegen, und zeichnet sich innerhalb von nützlicher Frist keine Besserung ab, kann die Rega die bodengebundene Rettungskolonne aufbieten. Sie steigt zu Fuss mit dem notwendigen Material zum Unfallort auf und unterstützt dich. Denke aber daran, dass je nach Standort Stunden vergehen können, bis die Helfer vor Ort sind.

Manchmal ist auch der improvisierte Transport einer verletzten Person notwendig. Dazu eignet sich die Rucksacktrage. Sie ist eine behelfsmässige Bahre, rasch hergestellt und benötigt nur eure Rucksäcke. Es werden je nach Grösse des Verletzten zwei oder drei Rucksäcke – nicht entleert – in einer Reihe auf den Boden gelegt und die Tragriemen miteinander verbunden. Der Patient kann nun darauf gelegt und von vier oder sechs Personen getragen werden.

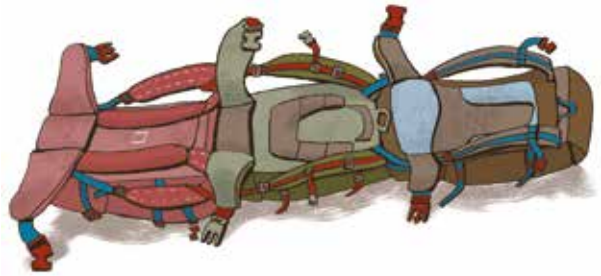

Glossar

Vereinsleitung	Verantwortliche Leiterperson der Schar, Abteilung, Ortsgruppe (Scharleitung, Abteilungsleitung), Vorstand, Komitee.
Lagerleitung	Verantwortliche Leitende für das Lager.
Jugendverband	Pfadi, Jubla, Cevi, Besj, Jemk und weitere kleine Verbände.
Jugendorganisation	Lokale Pfadiabteilung, lokale Schar, lokale Jungschar, Ortsgruppe.
Grobprogramm	Zusammengefasste Übersicht des Lagerprogramms in Tabellenform, eine andere Bezeichnung lautet «Picasso».
Höck	Sitzungen im Leitungsteam.
TN-Infoblatt	Teilnehmendeninformationsblatt, Gesundheitsblatt, Notfallblatt.
Kinder	5–10-Jährige, Teilnehmende der Zielgruppe Kindersport.
Jugendliche	10–20-Jährige, Teilnehmende der Zielgruppe Jugendsport.
LS/T	Lagersport/Trekking.
LS	Lagersport.
LA	Lageraktivität.
SPORTdb	Nationale Sportdatenbank.
Swisstopo	Schweizerische Landestopographie.
SLRG	Schweizerische Lebensrettungsgesellschaft.

Verwendete und weiterführende Literatur

Birrer, D., Ruchti, E., Morgan, G. (2010). *Psyche – Theoretische Grundlagen und praktische Beispiele.* Magglingen: BASPO.

Brunello, A.G., Walliser, M. & Hefti, U. (2010). *Gebirgs- und Outdoormedizin. Erste Hilfe, Rettung und Gesundheit unterwegs.* Bern: SAC Verlag.

Bundesamt für Sport (Hrsg.). *J+S-Notfallblatt.* Magglingen: BASPO.

Jaksic-Born, C. (2007). *Natura. Grundlagen der Biologie für Schweizer Maturitätsschulen.* Zug: Klett und Balmer Verlag.

Meier, R. (1995). *Bergsteigen mit Kindern. Anleitung für Erwachsene.* Bern: SAC-Verlag.

Mosimann, U. (2003). Unfälle Schweiz 2002. *bergundsteigen, 3/03,* 28–33.

Mutti, H.U. (2013). *Orientierungslauf – NORDA. Magglingen:* BASPO.

Swiss Forum for Sport Nutrition (Hrsg.). (2008). *Lebensmittelpyramide für Sportlerinnen und Sportler.* In Zusammenarbeit mit ETH Zürich und Bundesamt für Sport BASPO.

Volken, M. (2002). SAC lanciert neue Wanderskala, *Die Alpen 4/2002.* Bern: SAC-Verlag.

Volken, M. (2009). Die neuen «erfahrenen Bergwanderer», *Die Alpen 6/2009.* Bern: SAC-Verlag.

Autoren: Marco Gyger, Tobias Hug, Gaudenz Steinlin, Reto Züblin
Fachliche Beratung: Fachgruppe Lagersport/Trekking
Mitarbeit: Autorenteam J+S-Handbuch Lagersport/Trekking
Lektorat: Ueli Känzig

Foto: Erny Niederberger
Illustrationen: Sandra Gujer, Illuhouse, Biel/Bienne
Layout: Lernmedien EHSM

Ausgabe: 2014

Herausgeber: Bundesamt für Sport BASPO
Internet: www.baspo.ch, www.jugendundsport.ch
Bezugsquelle: dok.js@baspo.admin.ch
Bestell-Nr.: 30.401.530 d

Alle Rechte vorbehalten. Vervielfältigung oder Verbreitung jeder Art – auch auszugsweise – nur mit schriftlicher Genehmigung des Herausgebers und unter Quellenangabe gestattet.